जयपुर विकास प्राधिकरण, जयपुर।

ज.वि.प्रा. / अति.मु.न.नि. / बी.पी.सी.(बीपी) / 2020 / डी–1662 दिनांकः–04/12/2020

श्री नरेन्द्र सिंह,
अधिकृत हस्ताक्षरकर्ता,
आशियाना हाउसिंग लिमिटेड,
तृतीय तल, अपैक्स मॉल, लालकोठी,
टौंक रोड़, जयपुर।

विषयः– पुर्नगठित खसरा नम्बर 453, 454, 454/2, 454/1, 432, 433, 478, 479, 480, 484, 485, 434, 434/735, 435, 436, 437, 437/736, 438, 439, 440, 481, 482, 484, 500, 502, 503, 504/1, 478/716, ग्राम–झांई, तहसील–सांगानेर, महेन्द्रा सेज के पास, अजमेर रोड़, जयपुर के प्रस्तावित ग्रुप हाउसिंग के संशोधित भवन मानचित्र बाबत्।

महोदय,

आपका प्रार्थना पत्र दिनांक 12.11.2018 के संदर्भ में पुर्नगठित खसरा नम्बर 453, 454, 454/2, 454/1, 432, 433, 478, 479, 480, 484, 485, 434, 434/735, 435, 436, 437, 437/736, 438, 439, 440, 481, 482, 484, 500, 502, 503, 504/1, 478/716, ग्राम–झांई, तहसील–सांगानेर, महेन्द्रा सेज के पास, अजमेर रोड़, जयपुर में स्थित भूखण्ड (79,144.22 वर्गमीटर) पर 38.95 मीटर (बेसमेन्ट + स्टिल्ट + 12 तल) ऊँचाई के प्रस्तावित ग्रुप हाउसिंग के संशोधित भवन मानचित्र अनुमोदन के लिए प्रस्तुत किये गये थे, उनकी स्वीकृति भवन मानचित्र समिति (बीपी) की 226वीं बैठक दिनांक 28.05.2020 के निर्णयानुसार निम्न शर्तो के साथ दी जाती हैः–

1. यह भवन अनुज्ञा दिनांक 02.08.2025 (दिनांक 03.08.2018 को जारी संशोधित लीजडीड के अनुसार) तक प्रभावी है।
2. भवन निर्माण स्वीकृत मानचित्र के अनुसार ही किया जावेगा तथा किसी भी प्रकार का उल्लंघन (डेवियेशन) नहीं किया जायेगा।
3. भूखण्ड के स्वामी एवं मानचित्र तैयार करने वाले तकनीकीविज्ञ का कर्त्तव्य होगा कि वो यह सुनिश्चित कर ले कि स्वीकृति मानचित्र प्रचलित मास्टर प्लान/जोनल प्लान के अनुरूप है यदि कोई उल्लंघन जानकारी में नहीं है, प्राधिकरण को अधिकार होगा कि किसी स्थिति में उल्लंघन की जानकारी होने पर भवन मानचित्रों को दी गयी अनुज्ञा रद्द/बदली जा सकती है तथा प्रार्थी प्राधिकरण में किसी भी प्रकार की क्षतिपूर्ति का हकदार नहीं होगा।
4. एकीकृत भवन विनियम 2017 के विनियम संख्या 8.11.2 के अनुसार अपशिष्ठ जल का शुद्धिकरण एवं रिसाईकिलींग हेतु भवन विनियमों के प्रावधानों की पालना सुनिश्चित की जानी होगी।
5. एकीकृत भवन विनियम 2017 के विनियम संख्या 8.11.4 के अनुसार ठोस कचरा निस्तारण हेतु भवन विनियमों के प्रावधानों की पालना सुनिश्चित की जानी होगी।
6. एकीकृत भवन विनियम 2017 के विनियम संख्या 8.11.5 के अनुसार सौर ऊर्जा संयत्र संबंधी भवन विनियमों के प्रावधानों की पालना सुनिश्चित की जानी होगी।
7. एकीकृत भवन विनियम 2017 के विनियम संख्या 10.3 के अनुसार भवन में विद्युत आवश्यकताओं की पूर्ति हेतु संबंधित विद्युत वितरण एजेन्सी के प्रावधानों की पालना एवं एनर्जी कन्र्जेवेशन बिल्डिंग कोड के प्रावधानों की पालना सुनिश्चित की जानी होगी।
8. आप द्वारा एकीकृत भवन विनियम 2017 के विनियम संख्या 15.2 के अनुसार भवन निर्माण प्रारम्भ करते समय एक सूचना पट्ट मौके पर लगाया जायेगा। जिसमें संबंधित आयुक्त/उपायुक्त संबंधित जोन व प्रवर्तन अधिकारी के टेलीफोन नम्बर इत्यादि अंकित किये जाने होंगे व अनुमोदित मानचित्र की सूचना व अनुमोदन की शर्ते अंकित की जायेगी। निर्माण के दौरान अनुमोदित मानचित्र की एक प्रति आवश्यक रूप से निर्माणकर्ता द्वारा मौके पर रखी जायेगी।
9. निर्माण कार्य प्रारम्भ करने से पूर्व आप उपायुक्त जोन–11 प्राधिकरण को निर्धारित प्रपत्र में सूचना प्रस्तुत करेगे।
10. एकीकृत भवन विनियम 2017 के विनियम संख्या 15.5 के अनुसार भवन विनियम के अपेक्षाओं के अनुरूप भवन निर्माण करने की जिम्मेदारी भवन निर्माण अनुज्ञाधारी की होगी।
11. उक्त स्वीकृति के कारण यदि जयपुर विकास प्राधिकरण को किसी न्यायालय, सक्षम अधिकारी तथा नगर भूमि (अधिकतम सीमा एवं विनियम) अधिनियम के तहत नियुक्त अधिकारी के समक्ष किसी कार्यवाही में कोई भी खर्च, नुकसान, मुआवजा देना पडे या देने योग्य हो तो प्रार्थी उनकी इस क्षति को पूर्ण करने के लिए बाध्य होगा।
12. दरवाजे एवं खिड़कियाँ इस प्रकार लगाए जायेगें कि वो सडक की ओर निकले हुए नहीं हों।
13. भूस्वामी प्रत्येक मंजिल के लिए स्वीकृत आवासीय ईकाई से अधिक का निर्माण नहीं करेगा।
14. भूस्वामी भवन के परिसर को स्वीकृत उपयोग के अनुसार ही उपयोग में लेगा।
15. तकनीकीविज्ञ के निरीक्षण में स्वामी निर्माण कार्य करवायेगा जिसके संबंध में सूचना प्राधिकरण को पूर्व में देनी होगी। यदि तकनीकीविज्ञ को बदला जाता है तो इसकी सूचना 48 घन्टे के अन्दर यथोचित प्रमाण–पत्र में प्राधिकरण को देनी होगी।
16. आवेदक द्वारा पार्किंग क्षेत्र की पालना एकीकृत भवन विनियम 2017 के विनियम 10.1.16 के अनुसार सुनिश्चित की जानी होगी।
17. भवन परिसर में आगतुकों की पार्किंग करवाई जाए तथा आगंतुकों हेतु निःशुल्क वाहन पार्किंग का बोर्ड लगवाया जावे।

18. स्वीकृत मानचित्र मौके पर उपयुक्त स्थान पर बोर्ड लगाकर उस पर स्पष्ट रूप से दर्शाने होगें।
19. निर्माण स्थल पर स्वीकृति का विवरण अर्थात अनुमोदित मानचित्र, उपलब्ध पार्किंग की सूचना एवं भवन में सुरक्षा एवं निकास प्लान (Escape Plan) का नक्शा भी प्रदर्शित (Display) उपयुक्त स्थान पर प्रदर्शित किया जावें।
20. भवन का उपयोग प्रांरभ होने पर एक केयर टेकर की नियुक्ति की जावें जिसके पास भवन का मानचित्र, सुरक्षा एवं निकास प्लान (Escape Plan) उपलब्ध रहें। इस प्रकार नियुक्त केयर टेकर के मोबाईल नंबर एवं Land Line Number भी लिये जाकर पुलिस आयुक्त जयपुर महानगर व उपायुक्त जोन को सूचना उपलब्ध करवाई जावें ताकि किसी भी दुर्घटना की स्थिति में बचाव कार्य प्रभावी रूप से किये जा सकें।
21. एकीकृत भवन विनियम 2017 के विनियम संख्या 18.3 की अनुपालना में "गलत तथ्यों पर प्राप्त की गई अथवा तथ्यों को छुपाकर प्राप्त की गई स्वीकृति स्वत निरस्त मानी जायेगी एवं ऐसी निर्माण स्वीकृति प्राप्त करने के लिए आवेदनकर्ता को दोषी माना जायेगा।"
22. प्रश्नगत प्रकरण किसी भी न्यायालय में यदि लंबित है तो उसकी समस्त जिम्मेदारी आवेदक की ही होगी। यदि मानचित्र जारी होने के पश्चात यह अवगत हुआ कि किसी भी माननीय न्यायालय में प्रकरण लंबित है अथवा विपरीत निहित है तो मानचित्र स्वतः ही निरस्त समझे जावेंगें।
23. अनुमोदित भवन मानचित्रों को भवन निर्माण शुरू किये जाने के समय भवन निर्माता द्वारा एक बोर्ड पर सम्पूर्ण ब्यौरा सहित जो पठनीय हो, को ऐसे स्थल पर (मुख्य सड़क की ओर) लगाया जावे, जिससे सभी लोगों को निर्मित किये जाने वाले भवन के अनुमोदन की पूर्ण जानकारी प्राप्त हो सके।
24. भवन निर्माण के समय निर्माण सामग्री से आसपास के भवनों के निवासकर्ताओं को किसी प्रकार की असुविधा न हो, इस हेतु भवन निर्माण के दौरान चारों ओर पर्दे लगवाये जावें।
25. भवन मानचित्र इस शर्त के साथ जारी किये जाते है कि आप द्वारा परियोजना के पूर्णता प्रमाण पत्र के आवेदन के साथ पर्यावरण विभाग एवं अग्निशमन विभाग का अनापत्ति प्रमाण पत्र नगरीय निकाय में जमा कराना होगा, उसके पश्चात ही पूर्णता प्रमाण पत्र जारी किया जायेगा।
26. निर्मित भवन के प्रवेश द्वार के पास भवन में अनुमोदित व उपलब्ध चार पहिया व दो पहिया वाहनों के पार्किंग की सूचना का बोर्ड (डिस्पले) लगवाया जावें।
27. आप द्वारा Split location भूखण्ड़ संख्या 485, ग्राम भम्भोरिया, महिन्द्रा सेज, तहसील सांगानेर, जयपुर पर EWS/LIG का निर्माण मूल भूखण्ड़ की जारी की गई स्वीकृति की दिनांक से 2 वर्ष के भीतर तैयार कर सूचना जविप्रा को दी जानी होगी अन्यथा नियमानुसार कार्यवाही की जावेंगी।

संलग्नः– मानचित्रों की प्रति का 1 सेट (18 मानचित्र)

भवदीय,

(ओमप्रकाश पारीक)
अतिरिक्त मुख्य नगर नियोजक,
भवन मानचित्र समिति (बीपी)
जयपुर विकास प्राधिकरण, जयपुर।

प्रतिलिपिः– सूचनार्थ एवं आवश्यक कार्यवाही हेतु।

1. प्रबन्ध निदेशक, जयपुर विद्युत वितरण निगम लि0, विद्युत भवन जनपथ, जयपुर को सूचनार्थ प्रेषित है।
2. मुख्य अभियन्ता, मुख्यालय जन स्वाथ्य अभियांत्रिकी विभाग हसनपुरा रोड, रेल्वे हॉस्पीटल के पास, जयपुर को सूचनार्थ प्रेषित है।
3. रजिस्ट्रार, Rajasthan Real Estate Regulatory Authority, 2nd & 3rd Floor, RSIC Building, Udyog Bhavan, Tilak Marg, C-Scheme, Jaipur-302005 को सूचनार्थ प्रेषित हैं।
4. मुख्य नियन्त्रक (प्रर्वतन), जयपुर विकास प्राधिकरण, जयपुर को मानचित्रों की प्रति (18 मानचित्र) संलग्न कर अग्रिम कार्यवाही हेतु प्रेषित है।
5. श्री धर्मपाल सिंह, उपकर निर्धारण अधिकारी एवं संभागीय संयुक्त श्रम आयुक्त, शान्ति नगर, हसनपुरा, जयपुर को सूचनार्थ प्रेषित हैं।
6. उपायुक्त, जोन–11, जयपुर विकास प्राधिकरण, जयपुर को मानचित्रों की प्रति (18 मानचित्र) संलग्न कर अग्रिम कार्यवाही हेतु प्रेषित है।
7. उपायुक्त राजस्व–प्रथम, नगर निगम, जयपुर को पत्र क्रमांक एफ. 6()/उपा. रा (प्रथम)/जननि/2019/18 दिनांक 08.03.2019 के क्रम में सूचनार्थ प्रेषित हैं।

(ओमप्रकाश पारीक)
अतिरिक्त मुख्य नगर नियोजक,
भवन मानचित्र समिति (बीपी)
जयपुर विकास प्राधिकरण, जयपुर।

जयपुर विकास प्राधिकरण, जयपुर।

ज.वि.प्रा. / अति.मु.न.नि. / बी.पी.सी.(बीपी) / 2021 / डी–1572 दिनांकः– 29/11/2021

श्री नरेन्द्र सिंह,
अधिकृत हस्ताक्षरकर्ता,
आशियाना हाउसिंग लिमिटेड,
तृतीय तल, अपैक्स मॉल, लालकोठी,
टौंक रोड़, जयपुर।

विषयः– पुर्नगठित खसरा नम्बर 453, 454, 454/2, 454/1, 432, 433, 478, 479, 480, 484, 485, 434, 434/735, 435, 436, 437, 437/736, 438, 439, 440, 481, 482, 484, 500, 502, 503, 504/1, 478/716, ग्राम–झांई, तहसील–सांगानेर, महेन्द्रा सेज के पास, अजमेर रोड़, जयपुर के प्रस्तावित ग्रुप हाउसिंग के संशोधित भवन मानचित्र बाबत्।

महोदय,

आपका प्रार्थना पत्र दिनांक 12.11.2018 के संदर्भ में पुर्नगठित खसरा नम्बर 453, 454, 454/2, 454/1, 432, 433, 478, 479, 480, 484, 485, 434, 434/735, 435, 436, 437, 437/736, 438, 439, 440, 481, 482, 484, 500, 502, 503, 504/1, 478/716, ग्राम–झांई, तहसील–सांगानेर, महेन्द्रा सेज के पास, अजमेर रोड़, जयपुर में स्थित भूखण्ड (79,144.22 वर्गमीटर) पर 41.90 मीटर ऊँचाई के प्रस्तावित ग्रुप हाउसिंग के भवन मानचित्र अनुमोदन के लिए बीपीसी–बीपी की 226वीं बैठक दिनांक 28.05.2020 में प्रस्तुत किये गये थे। प्रश्नगत भूखण्ड़ की ऊँचाई 40 मीटर से अधिक होने के कारण प्रकरण राज्य सरकार को प्रेषित किया गया, राज्य सरकार से स्वीकृति प्राप्त होने में देरी होने के कारण विकासकर्ता द्वारा प्रार्थना पत्र प्रस्तुत कर निवेदन किया गया है कि राज्य सरकार से 40 मीटर ऊँचाई से अधिक की स्वीकृति आने तक 38.95 मीटर ऊँचाई तक के ग्रुप हाउसिंग प्रयोजनार्थ भवन मानचित्र जारी कर दिये जायें। विकासकर्ता द्वारा किये गये निवेदन के क्रम में 38.95 मीटर ऊँचाई (बेसमेन्ट + स्टिल्ट + प्रथम तल से 12 तल) तक के ग्रुप हाउसिंग प्रयोजनार्थ भवन मानचित्र दिनांक 04.12.2020 को जारी किये गये

वर्तमान में राज्य सरकार से 40 मीटर ऊँचाई से अधिक अर्थात 41.90 मीटर ऊँचाई की स्वीकृति दिनांक 10.09.2021 को प्राप्त हो चुकी हैं। अतः 41.90 मीटर ऊँचाई (बेसमेन्ट + स्टिल्ट + प्रथम तल से 13 तल) की भवन निर्माण स्वीकृति एवं भवन मानचित्र निम्न शर्तो के साथ जारी किये जाते हैः–

1. यह भवन अनुज्ञा दिनांक 02.08.2025 (दिनांक 03.08.2018 को जारी संशोधित लीजडीड के अनुसार) तक प्रभावी है।
2. भवन निर्माण स्वीकृत मानचित्र के अनुसार ही किया जावेगा तथा किसी भी प्रकार का उल्लंघन (डेवियेशन) नहीं किया जायेगा।
3. भूखण्ड के स्वामी एवं मानचित्र तैयार करने वाले तकनीकीविज्ञ का कर्त्तव्य होगा कि वो यह सुनिश्चित कर ले कि स्वीकृति मानचित्र प्रचलित मास्टर प्लान/जोनल प्लान के अनुरूप है यदि कोई उल्लंघन जानकारी में नहीं है, प्राधिकरण को अधिकार होगा कि किसी स्थिति में उल्लंघन की जानकारी होने पर भवन मानचित्रों को दी गयी अनुज्ञा रद्द/बदली जा सकती है तथा प्रार्थी प्राधिकरण में किसी भी प्रकार की क्षतिपूर्ति का हकदार नहीं होगा।
4. एकीकृत भवन विनियम 2017 के विनियम संख्या 8.11.2 के अनुसार अपशिष्ठ जल का शुद्धिकरण एवं रिसाईकिलींग हेतु भवन विनियमों के प्रावधानों की पालना सुनिश्चित की जानी होगी।
5. एकीकृत भवन विनियम 2017 के विनियम संख्या 8.11.4 के अनुसार ठोस कचरा निस्तारण हेतु भवन विनियमों के प्रावधानों की पालना सुनिश्चित की जानी होगी।
6. एकीकृत भवन विनियम 2017 के विनियम संख्या 8.11.5 के अनुसार सौर ऊर्जा संयत्र संबंधी भवन विनियमों के प्रावधानों की पालना सुनिश्चित की जानी होगी।
7. एकीकृत भवन विनियम 2017 के विनियम संख्या 10.3 के अनुसार भवन में विद्युत आवश्यकताओं की पूर्ति हेतु संबंधित विद्युत वितरण एजेन्सी के प्रावधानों की पालना एवं एनर्जी कन्र्जेवेशन बिल्डिंग कोड के प्रावधानों की पालना सुनिश्चित की जानी होगी।
8. आप द्वारा एकीकृत भवन विनियम 2017 के विनियम संख्या 15.2 के अनुसार भवन निर्माण प्रारम्भ करते समय एक सूचना पट्ट मौके पर लगाया जायेगा। जिसमें संबंधित आयुक्त/उपायुक्त संबंधित जोन व प्रवर्तन अधिकारी के टेलीफोन नम्बर इत्यादि अंकित किये जाने होंगे व अनुमोदित मानचित्र की सूचना व अनुमोदन की शर्ते अंकित की जायेगी। निर्माण के दौरान अनुमोदित मानचित्र की एक प्रति आवश्यक रूप से निर्माणकर्ता द्वारा मौके पर रखी जायेगी।
9. निर्माण कार्य प्रारम्भ करने से पूर्व आप उपायुक्त जोन–11 प्राधिकरण को निर्धारित प्रपत्र में सूचना प्रस्तुत करेगे।
10. एकीकृत भवन विनियम 2017 के विनियम संख्या 15.5 के अनुसार भवन विनियम के अपेक्षाओं के अनुरूप भवन निर्माण करने की जिम्मेदारी भवन निर्माण अनुज्ञाधारी की होगी।
11. उक्त स्वीकृति के कारण यदि जयपुर विकास प्राधिकरण को किसी न्यायालय, सक्षम अधिकारी तथा नगर भूमि (अधिकतम सीमा एवं विनियम) अधिनियम के तहत नियुक्त अधिकारी के समक्ष किसी कार्यवाही में कोई भी खर्च, नुकसान, मुआवजा देना पडे या देने योग्य हो तो प्रार्थी उनकी इस क्षति को पूर्ण करने के लिए बाध्य होगा।
12. दरवाजे एवं खिड़कियाँ इस प्रकार लगाए जायेगें कि वो सडक की ओर निकले हुए नहीं हों।
13. भूस्वामी प्रत्येक मंजिल के लिए स्वीकृत आवासीय ईकाई से अधिक का निर्माण नहीं करेगा।
14. भूस्वामी भवन के परिसर को स्वीकृत उपयोग के अनुसार ही उपयोग में लेगा।

15. तकनीकीविज्ञ के निरीक्षण में स्वामी निर्माण कार्य करवायेगा जिसके संबंध में सूचना प्राधिकरण को पूर्व में देनी होगी। यदि तकनीकीविज्ञ को बदला जाता है तो इसकी सूचना 48 घन्टे के अन्दर यथोचित प्रमाण–पत्र में प्राधिकरण को देनी होगी।
16. आवेदक द्वारा पार्किंग क्षेत्र की पालना एकीकृत भवन विनियम 2017 के विनियम 10.1.16 के अनुसार सुनिश्चित की जानी होगी।
17. भवन परिसर में आगतुकों की पार्किंग करवाई जाए तथा आगंतुकों हेतु निःशुल्क वाहन पार्किंग का बोर्ड लगवाया जावे।
18. स्वीकृत मानचित्र मौके पर उपयुक्त स्थान पर बोर्ड लगाकर उस पर स्पष्ट रूप से दर्शाने होगें।
19. निर्माण स्थल पर स्वीकृति का विवरण अर्थात अनुमोदित मानचित्र, उपलब्ध पार्किंग की सूचना एवं भवन में सुरक्षा एवं निकास प्लान (Escape Plan) का नक्शा भी प्रदर्शित (Display) उपयुक्त स्थान पर प्रदर्शित किया जावें।
20. भवन का उपयोग प्रांरभ होने पर एक केयर टेकर की नियुक्ति की जावें जिसके पास भवन का मानचित्र, सुरक्षा एवं निकास प्लान (Escape Plan) उपलब्ध रहें। इस प्रकार नियुक्त केयर टेकर के मोबाईल नंबर एवं Land Line Number भी लिये जाकर पुलिस आयुक्त जयपुर महानगर व उपायुक्त जोन को सूचना उपलब्ध करवाई जावें ताकि किसी भी दुर्घटना की स्थिति में बचाव कार्य प्रभावी रूप से किये जा सकें।
21. एकीकृत भवन विनियम 2017 के विनियम संख्या 18.3 की अनुपालना में "गलत तथ्यों पर प्राप्त की गई अथवा तथ्यों को छुपाकर प्राप्त की गई स्वीकृति स्वत निरस्त मानी जायेगी एवं ऐसी निर्माण स्वीकृति प्राप्त करने के लिए आवेदनकर्ता को दोषी माना जायेगा।"
22. प्रश्नगत प्रकरण किसी भी न्यायालय में यदि लंबित है तो उसकी समस्त जिम्मेदारी आवेदक की ही होगी। यदि मानचित्र जारी होने के पश्चात यह अवगत हुआ कि किसी भी माननीय न्यायालय में प्रकरण लंबित है अथवा विपरीत निहित है तो मानचित्र स्वतः ही निरस्त समझे जावेंगें।
23. अनुमोदित भवन मानचित्रों को भवन निर्माण शुरू किये जाने के समय भवन निर्माता द्वारा एक बोर्ड पर सम्पूर्ण ब्यौरा सहित जो पठनीय हो, को ऐसे स्थल पर (मुख्य सड़क की ओर) लगाया जावे, जिससे सभी लोगों को निर्मित किये जाने वाले भवन के अनुमोदन की पूर्ण जानकारी प्राप्त हो सके।
24. भवन निर्माण के समय निर्माण सामग्री से आसपास के भवनों के निवासकर्ताओं को किसी प्रकार की असुविधा न हो, इस हेतु भवन निर्माण के दौरान चारों ओर पर्दे लगवाये जावें।
25. भवन मानचित्र इस शर्त के साथ जारी किये जाते है कि आप द्वारा परियोजना के पूर्णता प्रमाण पत्र के आवेदन के साथ पर्यावरण विभाग एवं अग्निशमन विभाग का अनापत्ति प्रमाण पत्र नगरीय निकाय में जमा कराना होगा, उसके पश्चात ही पूर्णता प्रमाण पत्र जारी किया जायेगा।
26. निर्मित भवन के प्रवेश द्वार के पास भवन में अनुमोदित व उपलब्ध चार पहिया व दो पहिया वाहनों के पार्किंग की सूचना का बोर्ड (डिस्पले) लगवाया जावें।
27. आप द्वारा Split location भूखण्ड़ संख्या 485, ग्राम भम्भोरिया, महिन्द्रा सेज, तहसील सांगानेर, जयपुर पर EWS/LIG का निर्माण मूल भूखण्ड़ की जारी की गई स्वीकृति की दिनांक से 2 वर्ष के भीतर तैयार कर सूचना जविप्रा को दी जानी होगी अन्यथा नियमानुसार कार्यवाही की जावेंगी।

संलग्नः– मानचित्रों की प्रति का 1 सेट (19 मानचित्र)

भवदीय,

29/11/2024

वरिष्ठ नगर नियोजक,
भवन मानचित्र समिति (बीपी)
जयपुर विकास प्राधिकरण, जयपुर।

प्रतिलिपिः– सूचनार्थ एवं आवश्यक कार्यवाही हेतु।

1. मुख्य नियन्त्रक (प्रर्वतन), जयपुर विकास प्राधिकरण, जयपुर को मानचित्रों की प्रति (19 मानचित्र) संलग्न कर अग्रिम कार्यवाही हेतु प्रेषित है।
2. उपायुक्त, जोन–11, जयपुर विकास प्राधिकरण, जयपुर को मानचित्रों की प्रति (19 मानचित्र) संलग्न कर अग्रिम कार्यवाही हेतु प्रेषित है।
3. रजिस्ट्रार, Rajasthan Real Estate Regulatory Authority, 2nd & 3rd Floor, RSIC Building, Udyog Bhavan, Tilak Marg, C-Scheme, Jaipur-302005 को सूचनार्थ प्रेषित हैं।
4. निदेशक, राजस्थान राज्य विद्युत वितरण निगम लि0, विद्युत भवन जनपथ, जयपुर को सूचनार्थ प्रेषित है।
5. मुख्य अभियन्ता, मुख्यालय जन स्वाथ्य अभियांत्रिकी विभाग हसनपुरा रोड, रेल्वे हॉस्पीटल के पास, जयपुर को सूचनार्थ प्रेषित है।
6. उपायुक्त राजस्व–प्रथम, नगर निगम, जयपुर को पत्र क्रमांक एफ. 6()/उपा. रा (प्रथम)/जननि/2019/18 दिनांक 08.03.2019 के क्रम में सूचनार्थ प्रेषित हैं।

वरिष्ठ नगर नियोजक,
भवन मानचित्र समिति (बीपी)
जयपुर विकास प्राधिकरण, जयपुर।

SHEET NO. 01/18

AREA CALCULATIONS OF PREVIOUS APPROVED / EXISTING BUILDING BLOCKS

AREA CALCULATIONS OF PROPOSED BUILDING BLOCKS

PARKING FACILITY AREA CHART OF PREVIOUS APPROVED / EXISTING BUILDING BLOCKS

1. TOTAL B AR AREA CONSUMED IN PREVIOUS APPROVED / EXISTING BUILDING BLOCKS (RESIDENTIAL) = 109626.44 Sq.Mt
2. TOTAL B AR AREA CONSUMED IN PREVIOUS APPROVED / EXISTING BUILDING BLOCKS (COMMERCIAL) = 108.76 Sq.Mt
   a) ECU @ 115 SqM Required = 109626.44/ 115 = 953.27 E.C.U.
   b) Commercial ECU @ 75 SqM Required = 108.76 / 75 = 1.45 E.C.U.
3. TOTAL E.C.U.
   953.27 + 1.45 = 954.72 E.C.U. SAY 955E.C.U.

25% of Visitor parking (100) =25 nos
20% of Visitor parking (100) = 20 nos
15% of Visitor parking (100) = 15 nos
10% of Visitor parking (655) = 66 nos
say Total Visitor parking = 126 nos
Therefore Total ECU Req. (956 +126)= [illegible]

PARKING Req.
75% of car req(1082) = 812 Nos
25% of Two wheeler (1082) = 271 x 3 = 813 nos

4. PARKING PROVIDED IN PREVIOUS APPROVED BUILDING BLOCKS
CAR = 1100.00 Nos.
SCOOTERS = 1103.00 Nos.

PARKING FACILITY AREA CHART OF PROPOSED BUILDING BLOCKS

1. TOTAL B AR AREA CONSUMED = 53532.60 Sq.Mt
2. TOTAL COMMERCIAL B A R AREA = 754.57 Sq.Mt
3. TOTAL RESIDENTIAL B A R AREA =52778.76 SqM.
   a) ECU @ 115 SqM Required = 52778.76/ 115 = 458.94 ECU SAY=459 ECU
   b) Commercial ECU @ 75 SqM Required = 754.57 / 75 = 10.05 ECU SAY =10 ECU
4. TOTAL ECU Required :
   A. TOTAL Residential ECU = 459 ECU Req.
   25% of Visitor parking (100) =25 nos
   20% of Visitor parking (100) = 20 nos
   15% of Visitor parking (100) = 15 nos
   10% of Visitor parking (159) = 16 nos
   say Total Visitor parking = 76 nos
   Therefore Total ECU Req. (459+76)= 535 Nos
   B. Commercial ECU Required = 10 ECU Req.
   25% of Visitor parking =2.5 nos= 3nos
   Therefore Total ECU Req. (10+3)= 13 Nos

TOTAL ECU Required (Residential + Commercial)= 535+13= 548 nos

PARKING Req.
75% of car req(548) = 411 Nos
25% of Two wheeler (548) = 137 x 3 = 411 nos

5. PARKING PROVIDED FOR PROPOSED BUILDING BLOCKS
CAR = 646 Nos.
SCOOTERS = 198.00 Nos. / 66 ECU

AREA DETAILS:-

RECONSTITUTE AREA = 79,144.22 SqM
B.A.R. ALLOWABLE = 79,144.22 X 2.75 (2 +.75) = 2,17,646.60 SqM
ground coverage Achieved = 19.47 % (10,634. 74+4781.34 SqM)
Total Green Area Req. (79,144.22) = 15 % (11,871.633 SqM)
Total Green Area Provided. = 21.88% (9,476.75 +7840.69 SqM)
Maximum ground coverage alloweble(79144.22) = 35% (27,700.47 SqM)

(EWS & LIG PROPOSED)
Utilized B A R = 53,521.95 SqM.
5% of EWS & LIG S.Built Up Area Req = 2676.09 SqM

उक्त परियोजना हेतु आवश्यक EWS/LIG के आवास split Location में ... खसरा 485, ग्राम ... से, तहसील ... जयपुर पर प्रस्तावित है।
उपनगर नियोजक (BP)
जयपुर विकास प्राधिकरण, जयपुर

CLUB AREA = 1555.67SQ.MT.+141.37SQ.MT.+93.90SQ.MT. = 1790.94 SQ.MT.

tree req.
150 SqM. 1 tree req.
total plot area 79144.22 SqM.
say 79144.22 /150 = 341.42 Req.
say = 494.29 Req
provided = 500 nos

total green buffer area =16,598.965qM

GREEN AREA STATEMENT	
GREEN-1	4697.40 SqM.
GREEN-2	3143.29 SqM.
TOTAL	7840.69 sq.mt.

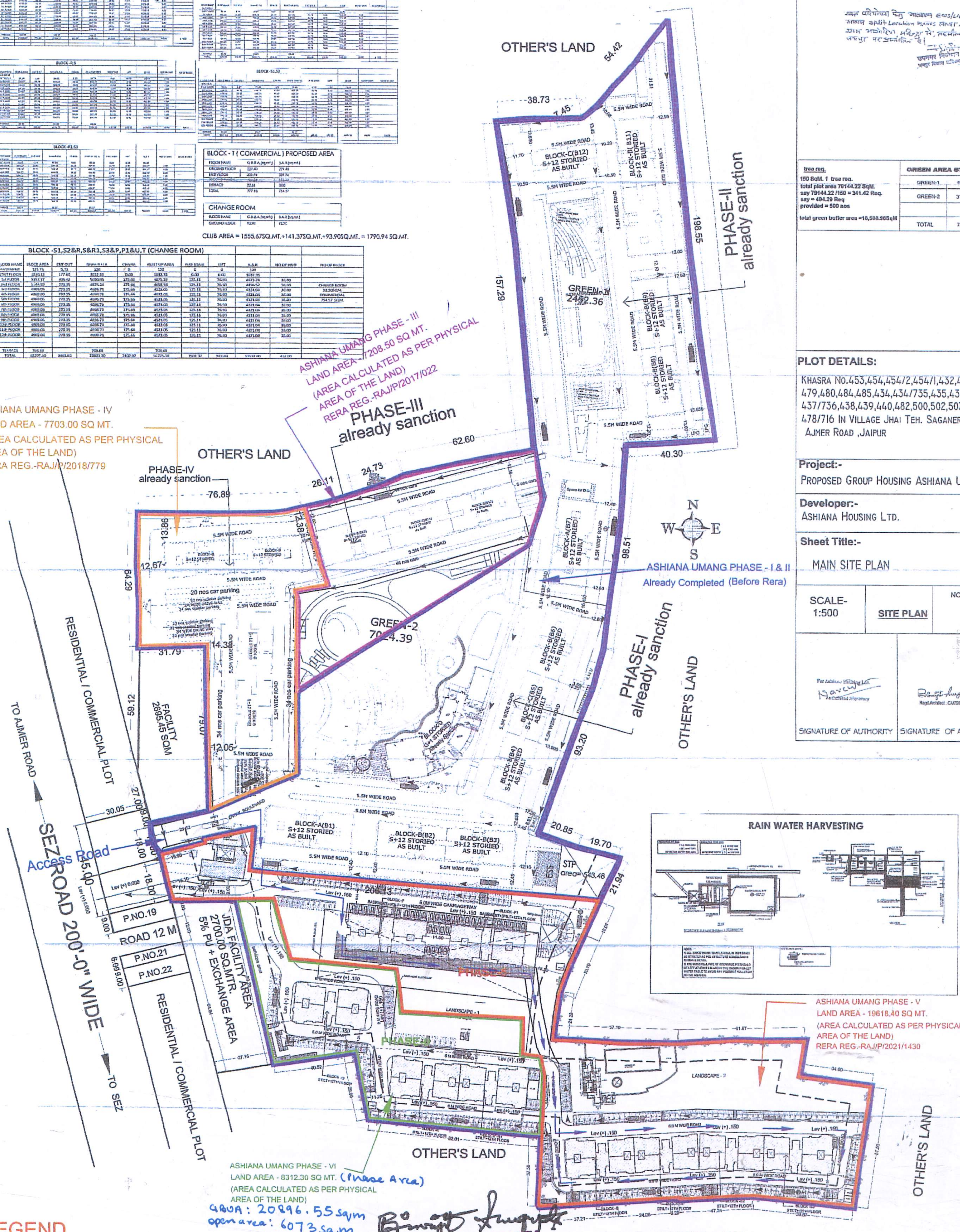

PLOT DETAILS:
KHASRA NO.453,454,454/2,454/1,432,433,478, 479,480,484,485,434,434/735,435,436,437, 437/736,438,439,440,482,500,502,503,504/1 478/716 IN VILLAGE JHAI TEH. SAGANER ON AJMER ROAD ,JAIPUR

Project:-
PROPOSED GROUP HOUSING ASHIANA UMANG

Developer:-
ASHIANA HOUSING LTD.

Sheet Title:-
MAIN SITE PLAN

SCALE- 1:500	SITE PLAN	NORTH

SIGNATURE OF AUTHORITY | SIGNATURE OF ARCHITECT

BISWAJIT SENGUPTA
B.Arch, FIIA, AIIID
Regd. Architect : CA/75/886

LEGEND

WHOLE PROJECT | ASHIANA UMANG PH-1&2 | ASHIANA UMANG PH-III | ASHIANA UMANG PH-IV | ASHIANA UMANG PH-V | ASHIANA UMANG PH-VI

PARKING FACILITY AREA CHART OF PREVIOUS APPROVED / EXISTING BUILDING BLOCKS

1. TOTAL B AR AREA CONSUMED IN PREVIOUS APPROVED / EXISTING BUILDING BLOCKS (RESIDENTIAL) = 109626.44 Sq.Mt
2. TOTAL B AR AREA CONSUMED IN PREVIOUS APPROVED / EXISTING BUILDING BLOCKS (COMMERCIAL) = 108.76 Sq.Mt
   a) ECU @ 115 SqM Required = 109626.44/ 115 = 953.27 E.C.U.
   b) Commercial ECU @ 75 SqM Required = 108.76 / 75 = 1.45 E.C.U.
3. TOTAL E.C.U.
953.27 + 1.45 = 954.72 E.C.U. SAY 955E.C.U.

25% of Visitor parking (100) =25 nos
20% of Visitor parking (100) = 20 nos
15% of Visitor parking (100) = 15 nos
10% of Visitor parking (655) = 66 nos
say Total Visitor parking = 126 nos
Therefore Total ECU Req. (956 +126)= 1082 Nos

PARKING Req.
75% of car req(1082) = 812 Nos
25% of Two wheeler.(1082) = 271 x 3 = 813 nos

4. PARKING PROVIDED IN PREVIOUS APPROVED BUILDING BLOCKS
CAR = 1100.00 Nos.
SCOOTERS = 1103.00 Nos.

PARKING FACILITY AREA CHART OF PROPOSED BUILDING BLOCKS

1. TOTAL B AR AREA CONSUMED = 53532.60 Sq.Mt
2. TOTAL COMMERCIAL B A R AREA = 754.57 Sq.Mt
3. TOTAL RESIDENTIAL B A R AREA =52778.76 SqM.
   a) ECU @ 115 SqM Required = 52778.76/ 115 = 458.94 ECU SAY=459 ECU
   b) Commercial ECU @ 75 SqM Required = 754.57 / 75 = 10.05 ECU SAY =10 ECU
4. TOTAL ECU Required :

A. TOTAL Residential ECU = 459 ECU Req.
25% of Visitor parking (100) =25 nos
20% of Visitor parking (100) = 20 nos
15% of Visitor parking (100) = 15 nos
10% of Visitor parking (159) = 16 nos
say Total Visitor parking = 76 nos
Therefore Total ECU Req. (459+76)= 535 Nos

B. Commercial ECU Required = 10 ECU Req.
25% of Visitor parking =2.5 nos= 3nos
Therefore Total ECU Req. (10+3)= 13 Nos

TOTAL ECU Required (Residential + Commercial)= 535+13= 548 nos

PARKING Req.
75% of car req(548) = 411 Nos
25% of Two wheeler (548) = 137 x 3 = 411 nos

5. PARKING PROVIDED FOR PROPOSED BUILDING BLOCKS
CAR = 646 Nos.
SCOOTERS = 198.00 Nos. / 66 ECU

PARKING PROVIDE

S.NO.	FLOOR	CAR	SCOOTER	TOTAL
1.	OPEN SPACE .	266 ECU	60 (20 ECU)	286 ECU
2.	STILT FLOOR	195 ECU	138 (46 ECU)	241 ECU
3.	BASEMENT FLOOR	185 ECU		185 ECU
	TOTAL E.C.U.	646 ECU	198 (66 ECU)	712 ECU

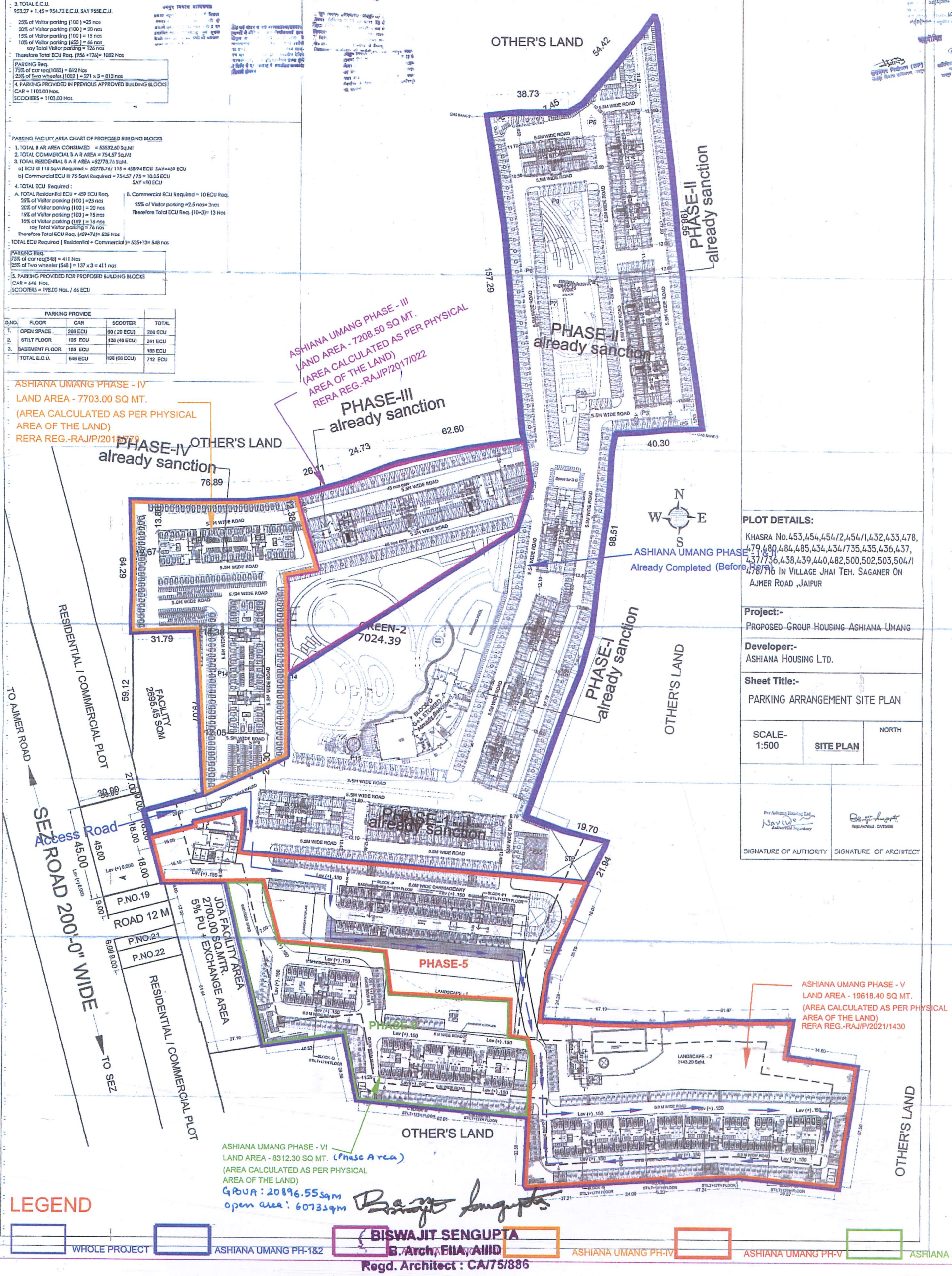

PLOT DETAILS:
KHASRA No.453,454,454/2,454/1,432,433,478, 479,480,484,485,434,434/735,435,436,437, 437/736,438,439,440,482,500,502,503,504/1 478/716 IN VILLAGE JHAI TEH. SAGANER ON AJMER ROAD ,JAIPUR

Project:-
PROPOSED GROUP HOUSING ASHIANA UMANG

Developer:-
ASHIANA HOUSING LTD.

Sheet Title:-
PARKING ARRANGEMENT SITE PLAN

SCALE- 1:500	SITE PLAN	NORTH
SIGNATURE OF AUTHORITY	SIGNATURE OF ARCHITECT	

SHEET NO. 01/18

AREA CALCULATIONS OF PREVIOUS APPROVED / EXISTING BUILDING BLOCKS

BLOCK - A

FLOOR	G.B.U.A. (sq.mt.)	B.A.R. (sq.mt.)
STILT FLOOR	654.83	85.12
TYPICAL (1st to 12th) FLOOR	654.83 x 12 = 7857.96 sq.mt.	626.55 x 12 = 7518.60 sq.mt.
TERRACE FLOOR	66.50	0.00
TOTAL	8579.29 sq.mt.	7603.72 sq.mt.
TOTAL NO. OF BLOCK - A = 2		
TOTAL	8579.29 x 2 = 17,158.58 sq.mt.	7603.72 x 2 = 15,207.44 sq.mt.

BLOCK - B

FLOOR	G.B.U.A. (sq.mt.)	B.A.R. (sq.mt.)
STILT FLOOR	483.59	84.54
TYPICAL (1st to 12th) FLOOR	483.59 x 12 = 5803.08 sq.mt.	456.19 x 12 = 5474.28 sq.mt.
TERRACE FLOOR	68.00	0.00
TOTAL	6354.67 sq.mt.	5558.82 sq.mt.
TOTAL NO. OF BLOCK - B = 14		
TOTAL	6354.67 x 14 = 88,965.38 sq.mt.	5558.82 x 14 = 77,823.48 sq.mt.

BLOCK - C

FLOOR	G.B.U.A. (sq.mt.)	B.A.R. (sq.mt.)
STILT FLOOR	439.65	84.55
TYPICAL (1st to 12th) FLOOR	439.65 x 12 = 5275.8 sq.mt.	410.73 x 12 = 4928.76 sq.mt.
TERRACE FLOOR	68.38	0.00
TOTAL	5783.83 sq.mt.	5013.31 sq.mt.
TOTAL NO. OF BLOCK - C = 3		
TOTAL	5783.83 x 3 = 17,351.49 sq.mt.	5013.31 x 3 = 15,039.93 sq.mt.

BLOCK - D (CLUB)

FLOOR	G.B.U.A. (sq.mt.)	B.A.R. (sq.mt.)
GROUND FLOOR	1316.87	1164.87
FIRST FLOOR	532.17	532.17
TOTAL	1848.84 sq.mt.	1697.04 sq.mt.

BLOCK - E (COMMERCIAL)

FLOOR	G.B.U.A. (sq.mt.)	B.A.R. (sq.mt.)
GROUND FLOOR	108.76 sq.mt.	108.76 sq.mt.

AREA CALCULATIONS OF BLOCK - A,B,C,D,E

BLOCK	G.B.U.A. (sq.mt.)	B.A.R. (sq.mt.)
BLOCK - A	17,158.58	15,207.44
BLOCK - B	88,965.38	77,823.48
BLOCK - C	17,351.49	15,039.93
BLOCK - D	1848.84	1697.04
BLOCK - E	108.76	108.76
TOTAL	1,25,433.05 sq.mt.	1,09,876.65 sq.mt.

PARKING FACILITY AREA CHART OF PREVIOUS APPROVED / EXISTING BUILDING BLOCKS

1. TOTAL B AR AREA CONSUMED IN PREVIOUS APPROVED / EXISTING BUILDING BLOCKS (RESIDENTIAL) = 109767.89 Sq.Mt
2. TOTAL B AR AREA CONSUMED IN PREVIOUS APPROVED / EXISTING BUILDING BLOCKS (COMMERCIAL) = 108.76 Sq.Mt
   a) ECU @ 115 SqM Required = 109767.89 / 115 = 954.50 E.C.U.
   b) Commercial ECU @ 75 SqM Required = 108.76 / 75 = 1.45 E.C.U.
3. TOTAL E.C.U.
   954.50 + 1.45 = 955.95 E.C.U. SAY 956 E.C.U.

25% of Visitor parking (100) =25 nos
20% of Visitor parking (100) = 20 nos
15% of Visitor parking (100) = 15 nos
10% of Visitor parking (656) = 66 nos
say Total Visitor parking = 126 nos
Therefore Total ECU Req. (956 +126)= 1082 Nos

PARKING Req.
75% of car req(1082) = 812 Nos
25% of Two wheeler.(1082) = 271 x 3 = 813 nos

4. PARKING PROVIDED IN PREVIOUS APPROVED BUILDING BLOCKS
CAR = 1100.00 Nos.
SCOOTERS = 1103.00 Nos.

Total ECU achieved - Old + New (2179.66)

PARKING FACILITY AREA CHART OF PROPOSED BUILDING BLOCKS

1. TOTAL B AR AREA CONSUMED = 57,619.63 Sq.Mt
2. TOTAL COMMERCIAL B A R AREA = 754.57 Sq.Mt
3. TOTAL RESIDENTIAL B A R AREA = 57,099.62 SqM.
   a) ECU @ 115 SqM Required = 57,099.62 / 115 = 496.51
   say = 497 nos
   b) Commercial ECU @ 75 SqM Required = 754.57 / 75 = 10.06

4. TOTAL ECU Required (497+10) = 507 ECU Req.

25% of Visitor parking (100) =25 nos
20% of Visitor parking (100) = 20 nos
15% of Visitor parking (100) = 15 nos
10% of Visitor parking (207) = 21 nos
say Total Visitor parking = 81 nos
Therefore Total ECU Req. (507+81)= 588 Nos

PARKING Req.
75% of car req(588) = 441 Nos
25% of Two wheeler.(588) = 147 x 3 = 441 nos

5. PARKING PROVIDED FOR PROPOSED BUILDING BLOCKS
CAR = 646 Nos.
SCOOTERS = 198.00 Nos.

AREA DETAILS:-

RECONSTITUTE **AREA = 79,144.22 SqM**
B.A.R. ALLOWABLE **= 79,144.22 X 2.75 (2 +.75) = 2,17,646.60 SqM**
Total Green Area Req. (79,144.22) = 15 % (11,871.633 SqM)
Green Area Provided on Podium = 3324.05 SqM (4.20%)
Green Area Provided in Open = 13454.51 SqM (17.0%)
Total Green Area Provided = 16778.56 SqM (21.19 %)

Maximum ground coverage alloweble(79144.22) = 35% (27,700.47 SqM)
ground coverage Achieved = (10,634. 74+4781.34 SqM)
= 19.47 % (15416.08 SqM)

(EWS & LIG PROPOSED)
Utilized B A R = 57,619.63 SqM.
5% of EWS & LIG S.Built Up Area Req = 2880.98 SqM

AREA CALCULATIONS OF PROPOSED BUILDING BLOCKS

BLOCK -P&P1

FLOOR NAME	BLOCK AREA	CUT OUT	Gross B.U.A	CHAJJA	BUILT UP AREA	FIRE STAIR	LIFT	B.A.R	NO OF UNIT	NO OF BLOCK
BASEMENT	125.73	5.73	120		120			120		
STILT FLOOR	139.71	6.82	132.89	0.00	132.89			132.89		
1st FLOOR	1292.87	68.19	1224.68	45.07	1184.61	28.65	17.68	1138.28	8.00	
2nd FLOOR	1292.87	68.19	1224.68	45.07	1184.61	28.65	17.68	1138.28	8.00	
3rd FLOOR	1292.87	68.19	1224.68	45.07	1184.61	28.65	17.68	1138.28	8.00	
4th FLOOR	1292.87	68.19	1224.68	45.07	1184.61	28.65	17.68	1138.28	8.00	
5th FLOOR	1292.87	68.19	1224.68	45.07	1184.61	28.65	17.68	1138.28	8.00	
6th FLOOR	1292.87	68.19	1224.68	45.07	1184.61	28.65	17.68	1138.28	8.00	
7th FLOOR	1292.87	68.19	1224.68	45.07	1184.61	28.65	17.68	1138.28	8.00	
8th FLOOR	1292.87	68.19	1224.68	45.07	1184.61	28.65	17.68	1138.28	8.00	
9th FLOOR	1292.87	68.19	1224.68	45.07	1184.61	28.65	17.68	1138.28	8.00	
10th FLOOR	1292.87	68.19	1224.68	45.07	1184.61	28.65	17.68	1138.28	8.00	
11th FLOOR	1292.87	68.19	1224.68	45.07	1184.61	28.65	17.68	1138.28	8.00	
12th FLOOR	1292.87	68.19	1224.68	45.07	1184.61	28.65	17.68	1138.28	8.00	
13th FLOOR	1292.87	68.19	1224.68	45.07	1184.61	28.65	17.68	1138.28	8.00	
TERRACE	148.99		148.99		148.99					
TOTAL	17221.74	834.02	16387.72	585.91	15803.81	372.45	229.94	15030.53	104.00	1 NOS

BLOCK -Q

FLOOR NAME	BLOCK AREA	CUT OUT	Gross B.U.A	CHAJJA	BUILT UP AREA	FIRE STAIR	LIFT	B.A.R	NO OF UNIT	NO OF BLOCK
BASEMENT										
STILT FLOOR	82.68	1.25	81.43	0.00	81.43			81.43		
1st FLOOR	591.15	31.81	559.33	21.75	537.58	13.78	8.66	515.34	4.00	
2nd FLOOR	591.15	31.82	559.33	21.75	537.58	13.78	8.66	515.34	4.00	
3rd FLOOR	591.15	31.82	559.33	21.75	537.58	13.78	8.66	515.34	4.00	
4th FLOOR	591.15	31.82	559.33	21.75	537.58	13.78	8.66	515.34	4.00	
5th FLOOR	591.15	31.82	559.33	21.75	537.58	13.78	8.66	515.34	4.00	
6th FLOOR	591.15	31.82	559.33	21.75	537.58	13.78	8.66	515.34	4.00	
7th FLOOR	591.15	31.82	559.33	21.75	537.58	13.78	8.66	515.34	4.00	
8th FLOOR	591.15	31.82	559.33	21.75	537.58	13.78	8.66	515.34	4.00	
9th FLOOR	591.15	31.82	559.33	21.75	537.58	13.78	8.66	515.34	4.00	
10th FLOOR	591.15	31.82	559.33	21.75	537.58	13.78	8.66	515.34	4.00	
11th FLOOR	591.15	31.82	559.33	21.75	537.58	13.78	8.66	515.34	4.00	
12th FLOOR	591.15	31.82	559.33	21.75	537.58	13.78	8.66	515.34	4.00	
13th FLOOR	591.15	31.82	559.33	21.75	537.58	13.78	8.66	515.34	4.00	
TERRACE	83.34		83.34		83.34					
TOTAL	7930.97	414.91	7516.06	282.75	7233.31	179.14	109.98	6780.85	52.00	1 NOS

BLOCK -R,S

FLOOR NAME	BLOCK AREA	CUT OUT	Gross B.U.A	CHAJJA	BUILT UP AREA	FIRE STAIR	LIFT	B.A.R	NO OF UNIT	NO OF BLOCK
BASEMENT										
STILT FLOOR	85.59	1.51	84.08	0.00	84.08	0.00	0.00	84.08	0.00	
1st FLOOR	534.07	29.78	504.29	39.55	464.74	13.78	8.66	462.50	4.00	
2nd FLOOR	534.07	29.78	504.29	39.55	464.74	13.78	8.66	462.50	4.00	
3rd FLOOR	534.07	29.78	504.29	39.55	464.74	13.78	8.66	462.50	4.00	
4th FLOOR	534.07	29.78	504.29	39.55	464.74	13.78	8.66	462.50	4.00	
5th FLOOR	534.07	29.78	504.29	39.55	464.74	13.78	8.66	462.50	4.00	
6th FLOOR	534.07	29.78	504.29	39.55	464.74	13.78	8.66	462.50	4.00	
7th FLOOR	534.07	29.78	504.29	39.55	464.74	13.78	8.66	462.50	4.00	
8th FLOOR	534.07	29.78	504.29	39.55	464.74	13.78	8.66	462.50	4.00	
9th FLOOR	534.07	29.78	504.29	39.55	464.74	13.78	8.66	462.50	4.00	
10th FLOOR	534.07	29.78	504.29	39.55	464.74	13.78	8.66	462.50	4.00	
11th FLOOR	534.07	29.78	504.29	39.55	464.74	13.78	8.66	462.50	4.00	
12th FLOOR	534.07	29.78	504.29	39.55	464.74	13.78	8.66	462.50	4.00	
13th FLOOR	534.07	29.78	504.29	39.55	464.74	13.78	8.66	462.50	4.00	
TERRACE	86.36		86.36		86.36					
TOTAL	7114.86	388.63	6726.21	254.15	6472.06	179.14	109.98	6096.58	52.00	2 NOS

BLOCK -S1,S2

FLOOR NAME	BLOCK AREA	CUT OUT	Gross B.U.A	CHAJJA	BUILT UP AREA	FIRE STAIR	LIFT	B.A.R	NO OF UNIT	NO OF BLOCK
BASEMENT										
STILT FLOOR	75.75	1.27	74.48	0.00	74.48	0.00	0.00	74.48		
1st FLOOR	474.43	28.38	446.05	15.32	430.73	13.78	8.66	408.49	4.00	
2nd FLOOR	474.43	28.38	446.05	15.32	430.73	13.78	8.66	408.49	4.00	
3rd FLOOR	474.43	28.38	446.05	15.32	430.73	13.78	8.66	408.49	4.00	
4th FLOOR	474.43	28.38	446.05	15.32	430.73	13.78	8.66	408.49	4.00	
5th FLOOR	474.43	28.38	446.05	15.32	430.73	13.78	8.66	408.49	4.00	
6th FLOOR	474.43	28.38	446.05	15.32	430.73	13.78	8.66	408.49	4.00	
7th FLOOR	474.43	28.38	446.05	15.32	430.73	13.78	8.66	408.49	4.00	
8th FLOOR	474.43	28.38	446.05	15.32	430.73	13.78	8.66	408.49	4.00	
9th FLOOR	474.43	28.38	446.05	15.32	430.73	13.78	8.66	408.49	4.00	
10th FLOOR	474.43	28.38	446.05	15.32	430.73	13.78	8.66	408.49	4.00	
11th FLOOR	474.43	28.38	446.05	15.32	430.73	13.78	8.66	408.49	4.00	
12th FLOOR	474.43	28.38	446.05	15.32	430.73	13.78	8.66	408.49	4.00	
13th FLOOR	474.43	28.38	446.05	15.32	430.73	13.78	8.66	408.49	4.00	
TERRACE	85.24		85.24		85.24					
TOTAL	6503.38	370.21	6133.17	199.16	5758.21	179.14	109.98	5464.85	52.00	2 NOS

BLOCK -R1,S3

FLOOR NAME	BLOCK AREA	CUT OUT	Gross B.U.A	CHAJJA	BUILT UP AREA	FIRE STAIR	LIFT	B.A.R	NO OF UNIT	NO OF BLOCK
BASEMENT										
STILT FLOOR	91.62	1.24	90.38	0.00	90.38	0.00	0.00	90.38		
1st FLOOR	534.02	29.51	504.51	39.55	464.96	13.78	8.66	462.72	4.00	
2nd FLOOR	534.02	29.51	504.51	39.55	464.96	13.78	8.66	462.72	4.00	
3rd FLOOR	534.02	29.51	504.51	39.55	464.96	13.78	8.66	462.72	4.00	
4th FLOOR	534.02	29.51	504.51	39.55	464.96	13.78	8.66	462.72	4.00	
5th FLOOR	534.02	29.51	504.51	39.55	464.96	13.78	8.66	462.72	4.00	
6th FLOOR	534.02	29.51	504.51	39.55	464.96	13.78	8.66	462.72	4.00	
7th FLOOR	534.02	29.51	504.51	39.55	464.96	13.78	8.66	462.72	4.00	
8th FLOOR	534.02	29.51	504.51	39.55	464.96	13.78	8.66	462.72	4.00	
9th FLOOR	534.02	29.51	504.51	39.55	464.96	13.78	8.66	462.72	4.00	
10th FLOOR	534.02	29.51	504.51	39.55	464.96	13.78	8.66	462.72	4.00	
11th FLOOR	534.02	29.51	504.51	39.55	464.96	13.78	8.66	462.72	4.00	
12th FLOOR	534.02	29.51	504.51	39.55	464.96	13.78	8.66	462.72	4.00	
13th FLOOR	534.02	29.51	504.51	39.55	464.96	13.78	8.66	462.72	4.00	
TERRACE	85.27		85.27		85.27					
TOTAL	7119.15	384.87	6734.28	254.15	6480.13	179.14	109.98	6105.74	52.00	2 NOS

BLOCK - T (COMMERCIAL) PROPOSED AREA

FLOOR NAME	G.B.U.A.(sq.mt.)	B.A.R.(sq.mt.)
GROUND FLOOR	229.40	229.40
FIRST FLOOR	339.94	339.94
SECOND FLOOR	185.23	185.23
TERRACE	22.61	0.00
TOTAL	777.18	754.57

Total Achieved club - (1697.04 + 93.90) 1790.94 m²

BLOCK - U (CHANGE ROOM)

FLOOR NAME	BLOCK AREA	CUT OUT	G.B.U.A	CHAJJA	B.U.A	FIRE STAIR	LIFT	B.A.R	NO OF BLOCK
BASEMENT									
G. FLOOR	219.52	125.62	93.90	0.00	93.90	0.00	0	93.90	
TOTAL	219.52	125.62	93.90	0.00	93.90	0.00	0.00	93.90	1 NOS

BLOCK -S1,S2&R,S&R1,S3&P,P1&U,Q,T (CHANGE ROOM)

FLOOR NAME	BLOCK AREA	CUT OUT	Gross B.U.A	CHAJJA	BUILT UP AREA	FIRE STAIR	LIFT	B.A.R	NO OF UNIT	NO OF BLOCK
BASEMENT	125.73	5.73	120	0	120	0	0	120		
STILT FLOOR	1149.26	141.73	1007.53	0.00	1007.53	0.00	0.00	1007.53		
1st FLOOR	5353.01	335.72	5017.29	175.66	4841.63	125.11	76.90	4639.62	36.00	
2nd FLOOR	4969.06	270.35	4698.71	175.66	4523.05	125.11	76.90	4321.04	36.00	CHANGE ROOM
3rd FLOOR	4969.06	270.35	4698.71	175.66	4523.05	125.11	76.90	4321.04	36.00	93.90SQM.
4th FLOOR	4969.06	270.35	4698.71	175.66	4523.05	125.11	76.90	4321.04	36.00	COMMERCIAL
5th FLOOR	4969.06	270.35	4698.71	175.66	4523.05	125.11	76.90	4321.04	36.00	520.01 SQM.
6th FLOOR	4969.06	270.35	4698.71	175.66	4523.05	125.11	76.90	4321.04	36.00	
7th FLOOR	4969.06	270.35	4698.71	175.66	4523.05	125.11	76.90	4321.04	36.00	
8th FLOOR	4969.06	270.35	4698.71	175.66	4523.05	125.11	76.90	4321.04	36.00	
9th FLOOR	4969.06	270.35	4698.71	175.66	4523.05	125.11	76.90	4321.04	36.00	
10th FLOOR	4969.06	270.35	4698.71	175.66	4523.05	125.11	76.90	4321.04	36.00	
11th FLOOR	4969.06	270.35	4698.71	175.66	4523.05	125.11	76.90	4321.04	36.00	
12th FLOOR	4969.06	270.35	4698.71	175.66	4523.05	125.11	76.90	4321.04	36.00	
13th FLOOR	4969.06	270.35	4698.71	175.66	4523.05	125.11	76.90	4321.04	36.00	
TERRACE	763.90		763.90		763.90					
TOTAL	67020.62	3727.38	63293.24	2283.58	61009.66	1626.43	999.70	57619.63	468.00	10 NOS

Q.B.U.A. OF PREVIOUS APPROVED / EXISTING BUILDINGS BLOCKS= 1,25,139.98 Sq.M.
F.A.R. OF PREVIOUS APPROVED / EXISTING BUILDINGS BLOCKS= 87,479.98 Sq.M.

Q.B.U.A. OF PREVIOUS APPROVED / EXISTING BUILDINGS BLOCKS= 1,25,433.05 Sq.M.
B.A.R. OF PREVIOUS APPROVED / EXISTING BUILDINGS BLOCKS= 1,09,876.65 Sq.M.

TOTAL Q.B.U.A. OF EXISTING AND PROPOSED BUILDINGS BLOCKS= 1,88,726.29 Sq.M.
TOTAL B.A.R. OF EXISTING AND PROPOSED BUILDINGS BLOCKS= 1,67,496.28 Sq.M. (2·116)

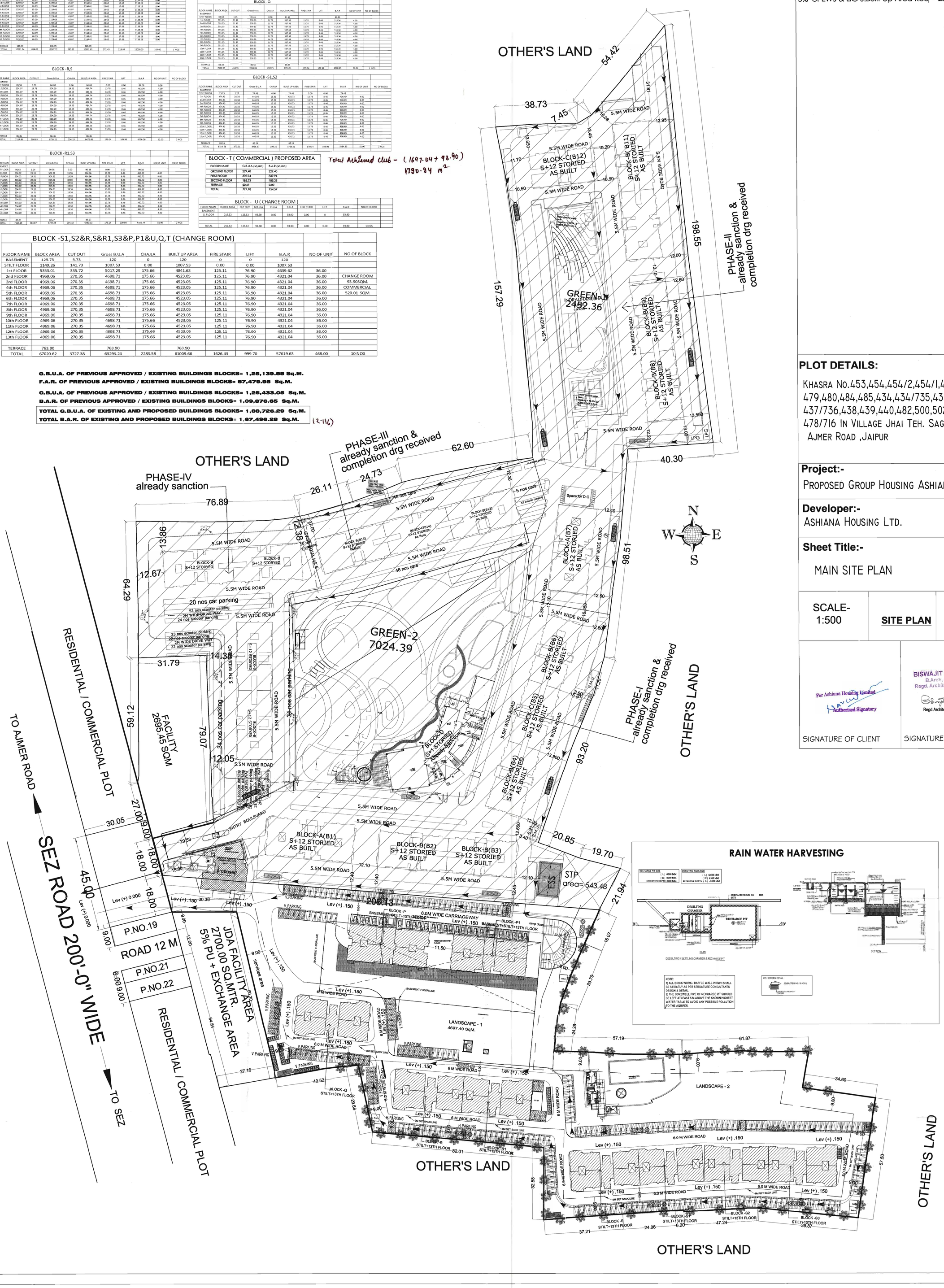

PLOT DETAILS:

KHASRA NO.453,454,454/2,454/1,432,433,478, 479,480,484,485,434,434/735,435,436,437, 437/736,438,439,440,482,500,502,503,504/1 478/716 IN VILLAGE JHAI TEH. SAGANER ON AJMER ROAD ,JAIPUR

Project:-
PROPOSED GROUP HOUSING ASHIANA UMANG

Developer:-
ASHIANA HOUSING LTD.

Sheet Title:-
MAIN SITE PLAN

SCALE- 1:500	SITE PLAN	NORTH

For Ashiana Housing Limited
Authorised Signatory
SIGNATURE OF CLIENT

BISWAJIT SENGUPTA
B.Arch, FIIA, AIIID
Regd. Architect : CA/75/886
Regd.Architect : CA/75/886
SIGNATURE OF ARCHITECT

PARKING FACILITY AREA CHART OF PREVIOUS APPROVED / EXISTING BUILDING BLOCKS

1. TOTAL B AR AREA CONSUMED IN PREVIOUS APPROVED / EXISTING BUILDING BLOCKS (RESIDENTIAL) = 109767.89 Sq.Mt
2. TOTAL B AR AREA CONSUMED IN PREVIOUS APPROVED / EXISTING BUILDING BLOCKS (COMMERCIAL) = 108.76 Sq.Mt
   a) ECU @ 115 SqM Required = 109767.89 / 115 = 954.50 E.C.U.
   b) Commercial ECU @ 75 SqM Required = 108.76 / 75 = 1.45 E.C.U.
3. TOTAL E.C.U.
954.50 + 1.45 = 955.95 E.C.U. SAY 956 E.C.U.

25% of Visitor parking (100) =25 nos
20% of Visitor parking (100) = 20 nos
15% of Visitor parking (100) = 15 nos
10% of Visitor parking (656) = 66 nos
say Total Visitor parking = 126 nos
Therefore Total ECU Req. (956 +126)= 1082 Nos

PARKING Req.
75% of car req(1082) = 812 Nos
25% of Two wheeler.(1082) = 271 x 3 = 813 nos

4. PARKING PROVIDED IN PREVIOUS APPROVED BUILDING BLOCKS
CAR = 1100.00 Nos.
SCOOTERS = 1103.00 Nos.

PARKING FACILITY AREA CHART OF PROPOSED BUILDING BLOCKS

1. TOTAL B AR AREA CONSUMED = 57,619.63 Sq.Mt
2. TOTAL COMMERCIAL B A R AREA = 754.57 Sq.Mt
3. TOTAL RESIDENTIAL B A R AREA = 57,099.62 SqM.
   a) ECU @ 115 SqM Required = 57,099.62 / 115 = 496.51
   say = 497 nos
   b) Commercial ECU @ 75 SqM Required = 754.57 / 75 = 10.06

4. TOTAL ECU Required (497+10) = 507 ECU Req.

25% of Visitor parking (100) =25 nos
20% of Visitor parking (100) = 20 nos
15% of Visitor parking (100) = 15 nos
10% of Visitor parking (207) = 21 nos
say Total Visitor parking = 81 nos
Therefore Total ECU Req. (507+81)= 588 Nos

PARKING Req.
75% of car req(588) = 441 Nos
25% of Two wheeler.(588) = 147 x 3 = 441 nos

5. PARKING PROVIDED FOR PROPOSED BUILDING BLOCKS
CAR = 646 Nos.
SCOOTERS = 198.00 Nos.

PARKING PROVIDE				
S.NO.	FLOOR	CAR	SCOOTER	TOTAL
1.	OPEN SPACE .	266 ECU	60 (20 ECU)	326 ECU
2.	STILT FLOOR	195 ECU	138 (46 ECU)	333 ECU
3.	BASEMENT FLOOR	185 ECU		185 ECU
	TOTAL E.C.U.	646 ECU	198 (66 ECU)	844 ECU

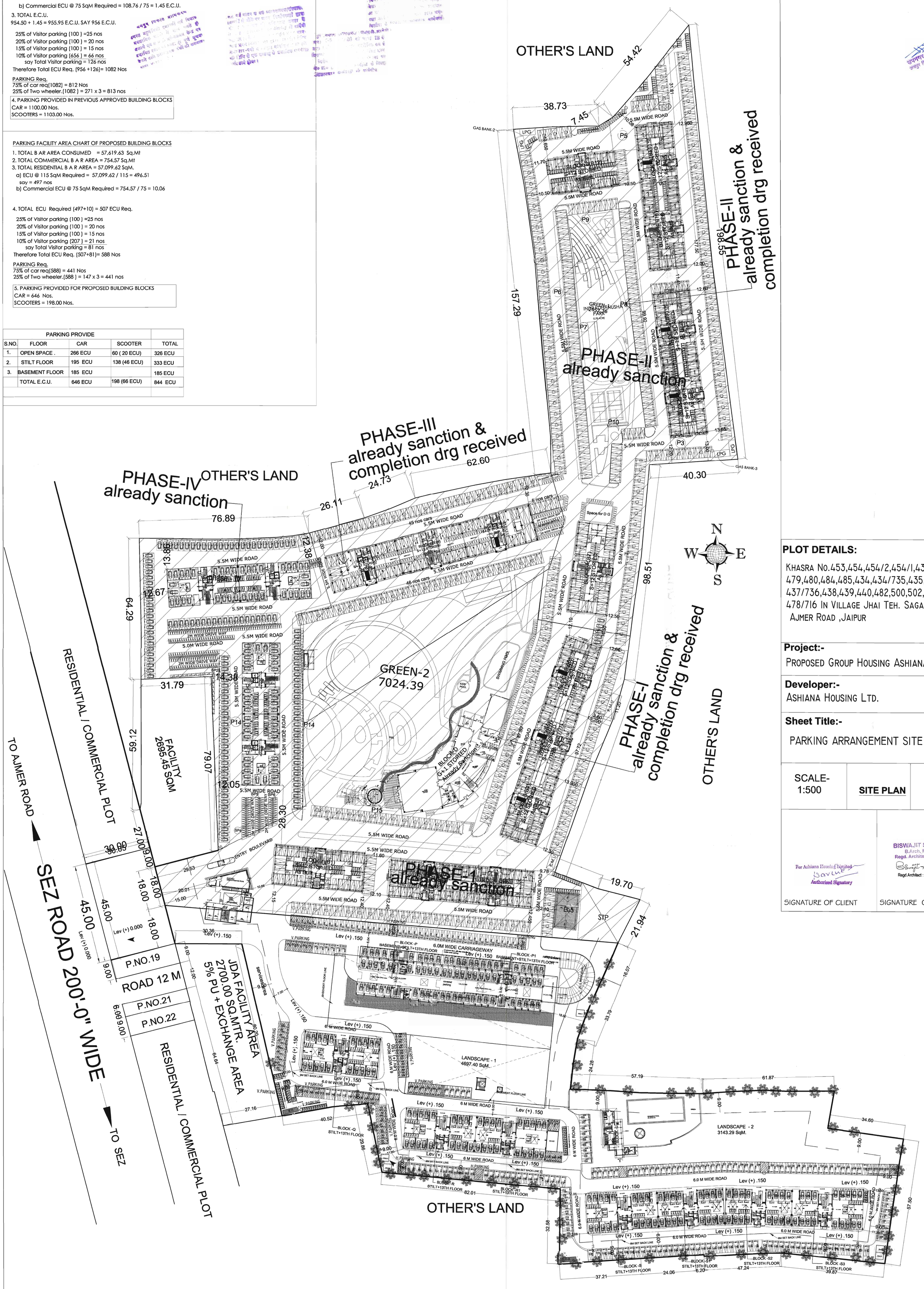

SHEET NO. 02/18

PLOT DETAILS:

KHASRA NO.453,454,454/2,454/1,432,433,478, 479,480,484,485,434,434/735,435,436,437, 437/736,438,439,440,482,500,502,503,504/1 478/716 IN VILLAGE JHAI TEH. SAGANER ON AJMER ROAD ,JAIPUR

Project:-
PROPOSED GROUP HOUSING ASHIANA UMANG

Developer:-
ASHIANA HOUSING LTD.

Sheet Title:-
PARKING ARRANGEMENT SITE PLAN

SCALE- 1:500	SITE PLAN	NORTH

For Ashiana Housing Limited
Authorised Signatory
SIGNATURE OF CLIENT

BISWAJIT SENGUPTA
B.Arch, FIIA, AIIID
Regd. Architect : CA/75/886
Regd.Architect : CA/75/886
SIGNATURE OF ARCHITECT



SHEET NO.04/18

PLOT DETAILS:

KHASRA NO.453,454,454/2,454/1,432,433,478, 479,480,484,485,434,434/735,435,436,437, 437/736,438,439,440,482,500,502,503,504/1 478/716 IN VILLAGE JHAI TEH. SAGANER ON AJMER ROAD ,JAIPUR

Project:-

PROPOSED GROUP HOUSING ASHIANA UMANG

Developer:-

ASHIANA HOUSING LTD.

Sheet title:-

BASEMENT FLOOR PLAN
STILT FLOOR PLAN

SCALE-1:100 | **BLOCK-P&P1 RESIDENCE** | NORTH variable/site plan

For Ashiana Housing Limited
Authorised Signatory
SIGNATURE OF CLIENT

BISWAJIT SENGUPTA
B.Arch, FIIA, AIIID
Regd. Architect : CA/75/886
Regd.Architect : CA/75/886
SIGNATURE OF ARCHITECT

SHEET NO. 03/18

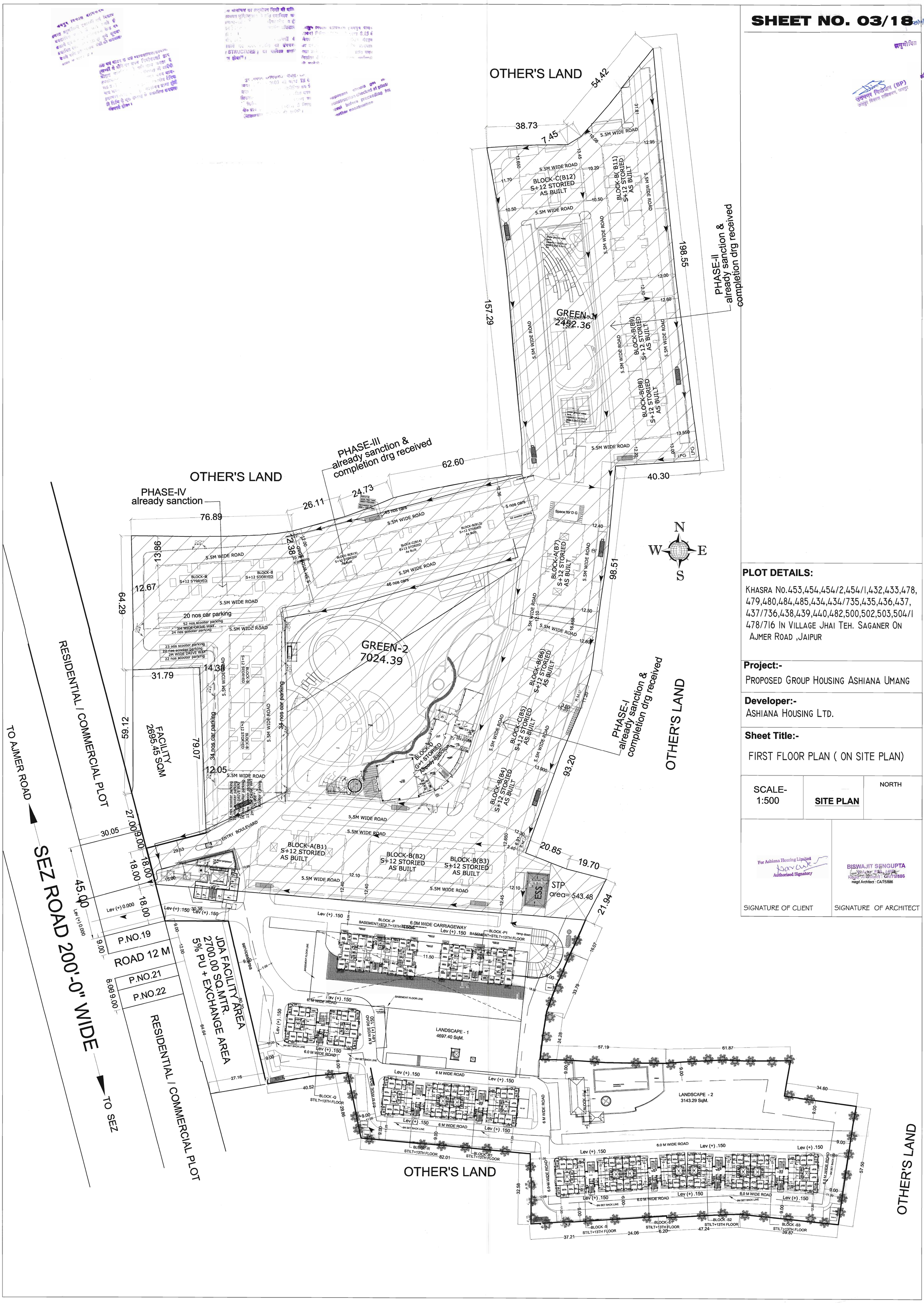

PLOT DETAILS:

KHASRA NO.453,454,454/2,454/1,432,433,478, 479,480,484,485,434,434/735,435,436,437, 437/736,438,439,440,482,500,502,503,504/1 478/716 IN VILLAGE JHAI TEH. SAGANER ON AJMER ROAD ,JAIPUR

Project:-

PROPOSED GROUP HOUSING ASHIANA UMANG

Developer:-

ASHIANA HOUSING LTD.

Sheet Title:-

FIRST FLOOR PLAN (ON SITE PLAN)

SCALE- 1:500	SITE PLAN	NORTH

For Ashiana Housing Limited
Authorised Signatory

SIGNATURE OF CLIENT

BISWAJIT SENGUPTA
Regd.Architect : CA/75/886

SIGNATURE OF ARCHITECT



SECTION ON B-B

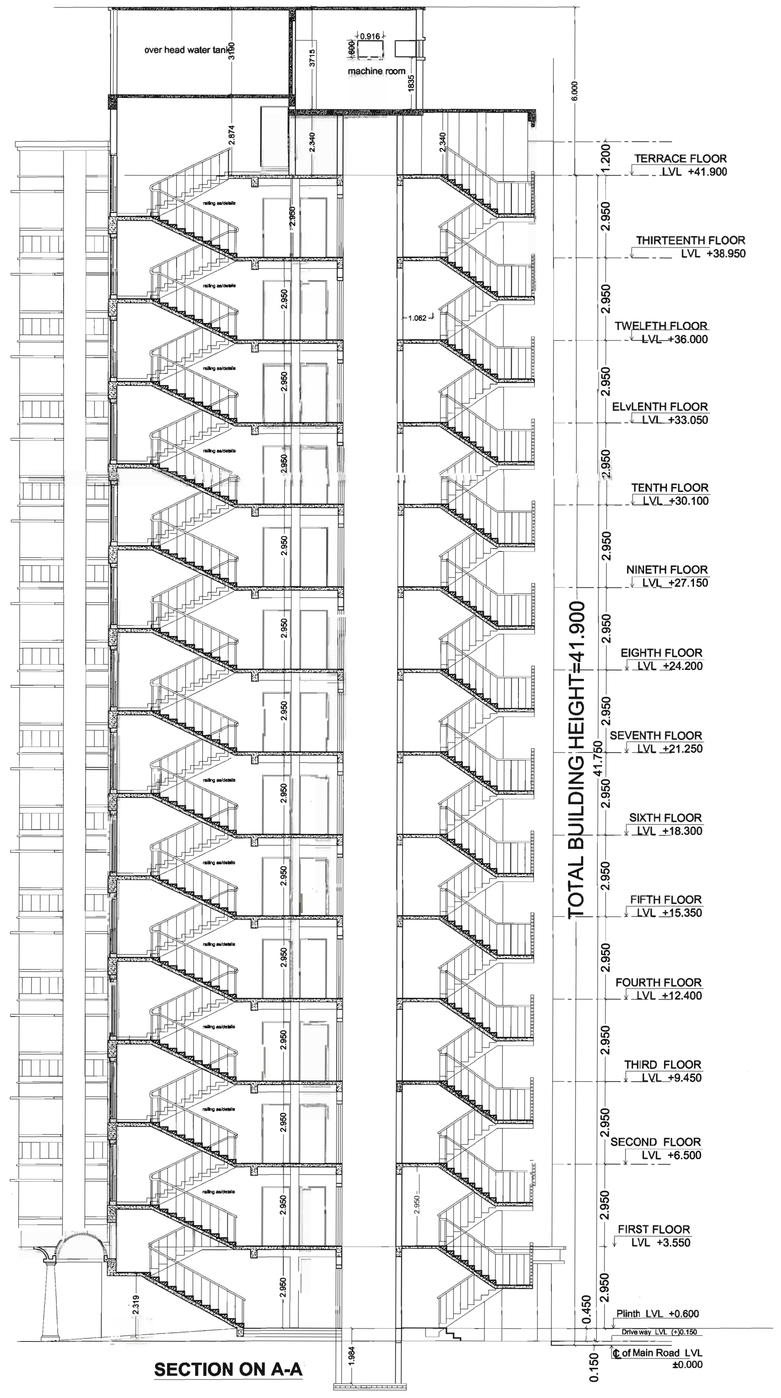

SECTION ON A-A

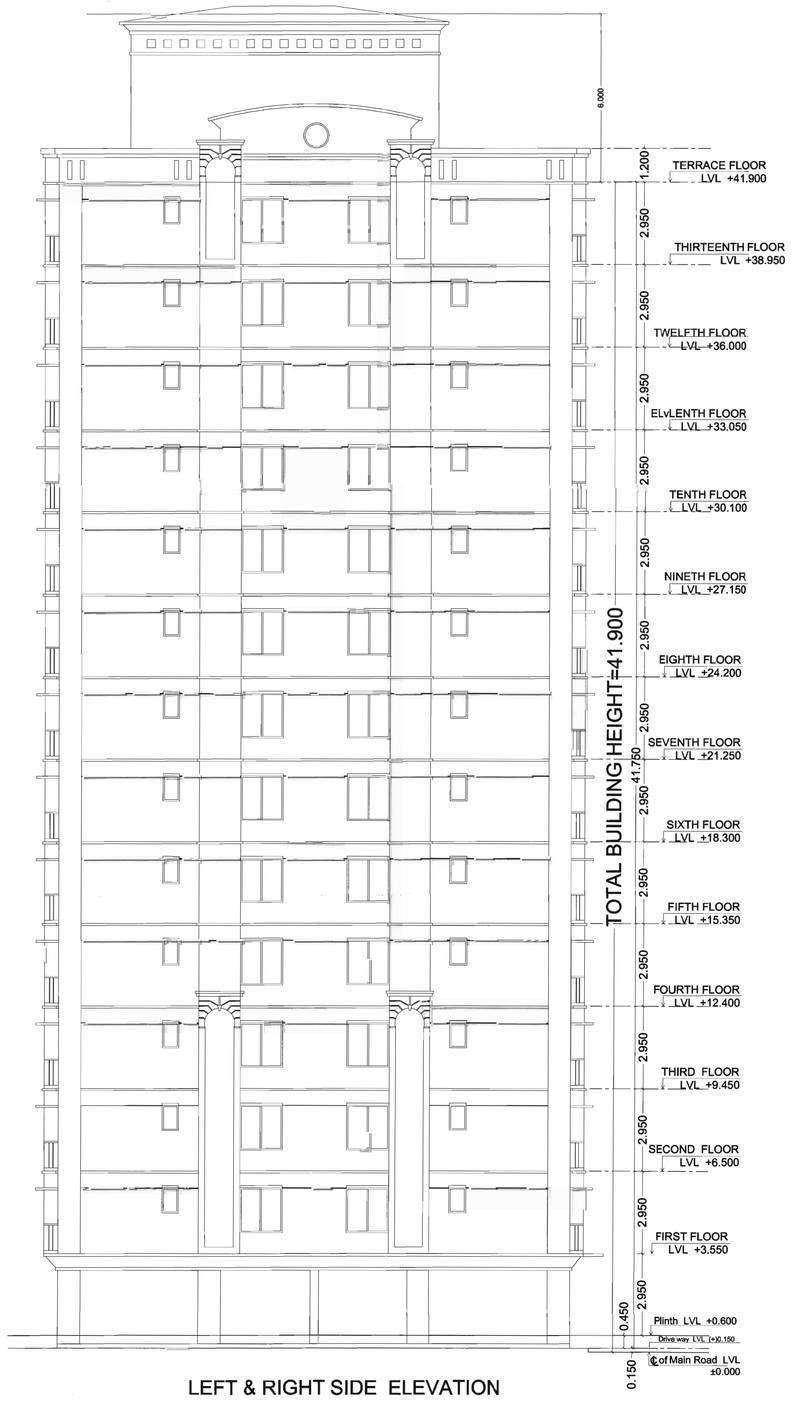

LEFT & RIGHT SIDE ELEVATION

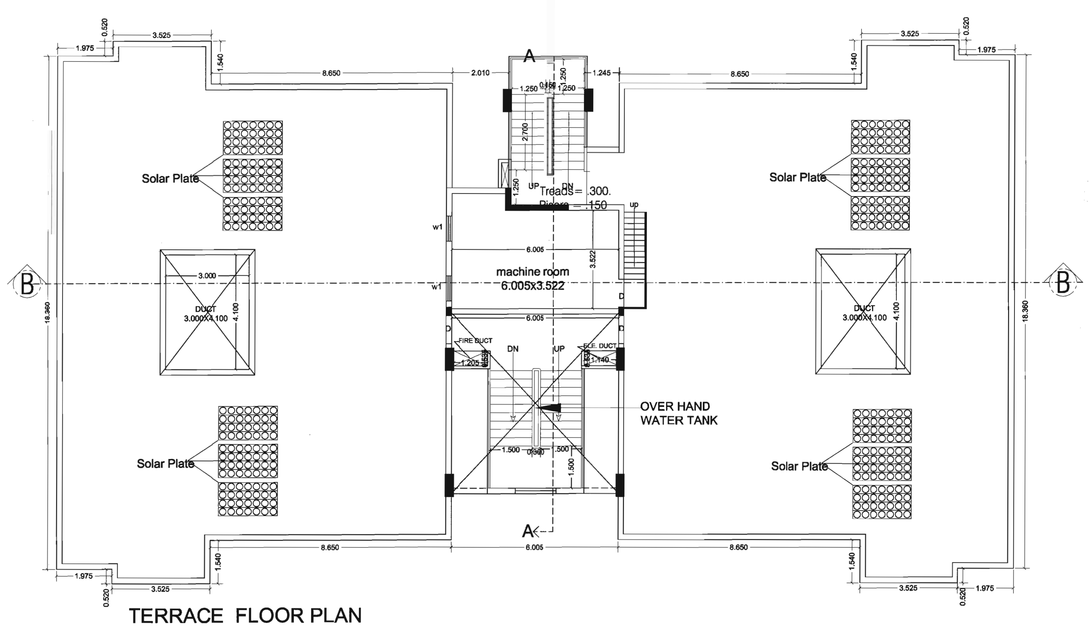

TERRACE FLOOR PLAN

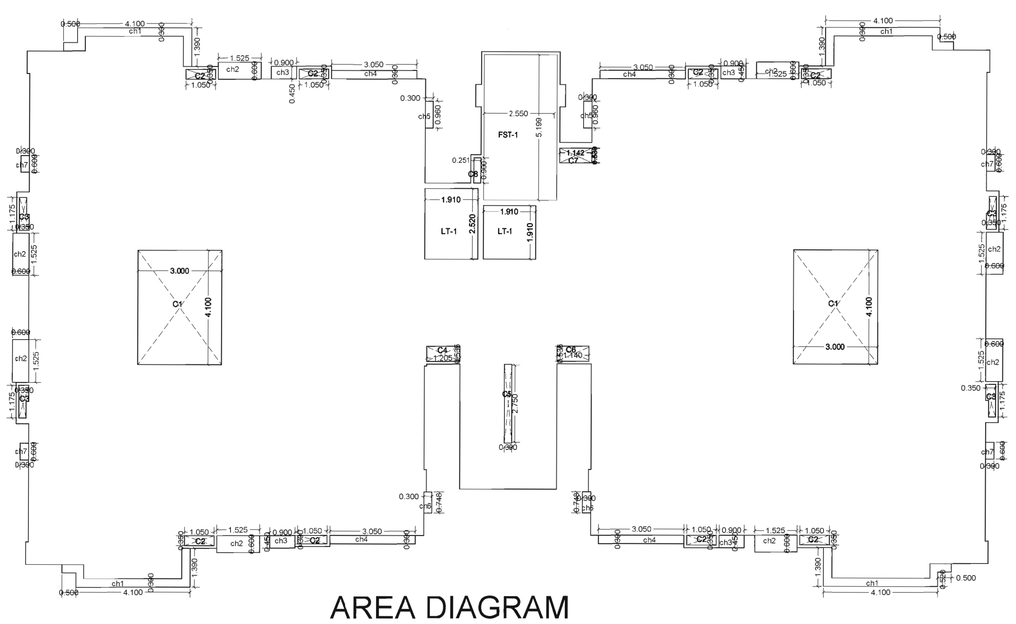

AREA DIAGRAM

BLOCK -Q

FLOOR NAME	BLOCK AREA	CUT OUT	Gross B.U.A	CHARJ	BUILT UP AREA	FIRE STAIR	LIFT	B.A.R	NO OF UNIT	NO OF BLOCK	
BASEMENT											
TER FLOOR	82.68	1.2%	81.43	0.00	81.43			81.43			
1st FLOOR	585.2%	31.82	553.38	21.2%	553.38	13.38	8.46	525.34	4.00		
2nd FLOOR	585.2%	31.82	553.38	21.2%	553.38	13.38	8.46	525.34	4.00		
3rd FLOOR	585.2%	31.82	553.38	21.2%	553.38	13.38	8.46	525.34	4.00		
4th FLOOR	585.2%	31.82	553.38	21.2%	553.38	13.38	8.46	525.34	4.00		
5th FLOOR	585.2%	31.82	553.38	21.2%	553.38	13.38	8.46	525.34	4.00		
6th FLOOR	585.2%	31.82	553.38	21.2%	553.38	13.38	8.46	525.34	4.00		
7th FLOOR	585.2%	31.82	553.38	21.2%	553.38	13.38	8.46	525.34	4.00		
8th FLOOR	585.2%	31.82	553.38	21.2%	553.38	13.38	8.46	525.34	4.00		
9th FLOOR	585.2%	31.82	553.38	21.2%	553.38	13.38	8.46	525.34	4.00		
10th FLOOR	585.2%	31.82	553.38	21.2%	553.38	13.38	8.46	525.34	4.00		
11th FLOOR	585.2%	31.82	553.38	21.2%	553.38	13.38	8.46	525.34	4.00		
12th FLOOR	585.2%	31.82	553.38	21.2%	553.38	13.38	8.46	525.34	4.00		
13th FLOOR	585.2%	31.82	553.38	21.2%	553.38	13.38	8.46	525.34	4.00		
TERRACE	83.34		83.34		83.34						
TOTAL	8782.57	414.91	8368.66	282.75	7751.11	178.14	118.58	6782.35	52.00	1 NOS.	

SHEET NO.09/18

PLOT DETAILS:

KHASRA NO.453,454,454/2,454/1,432,433,478, 479,480,484,485,434,434/735,435,436,437, 437/736,438,439,440,482,500,502,503,504/1 478/716 IN VILLAGE JHAI TEH. SAGANER ON AJMER ROAD ,JAIPUR

Project:-

PROPOSED GROUP HOUSING ASHIANA UMANG

Developer:-

ASHIANA HOUSING LTD.

Sheet title:-

TERRACE FLOOR PLAN
AREA DIAGRAM
ELEVATIONS & SECTION

SCALE-1:100

BLOCK- Q RESIDENCE

NORTH variable/site plan

For Ashiana Housing Limited
Authorised Signatory

BISWAJIT SENGUPTA
B.Arch. FIA, AIID
Regd. Architect : CA/75/886

Regd.Architect : CA/75/886

SIGNATURE OF CLIENT

SIGNATURE OF ARCHITECT

SHEET NO.10/18

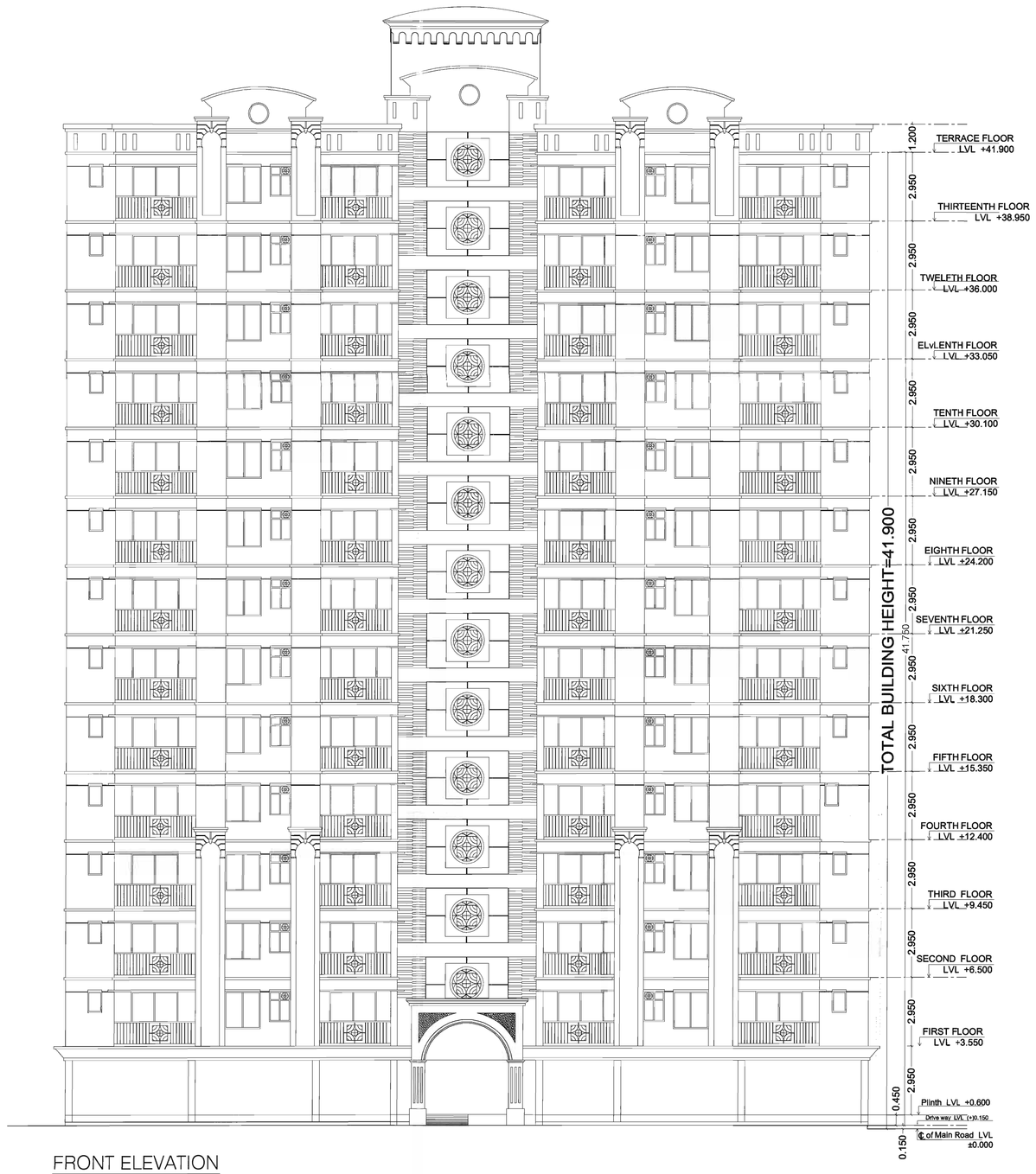

FRONT ELEVATION

REAR SIDE ELEVATION

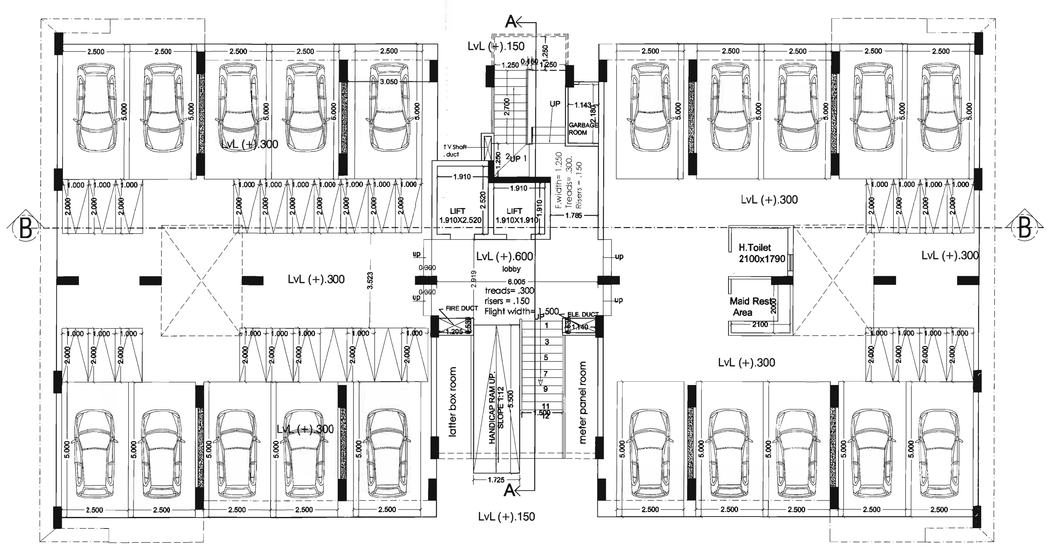

STILT FLOOR PLAN (BLOCK-Q)

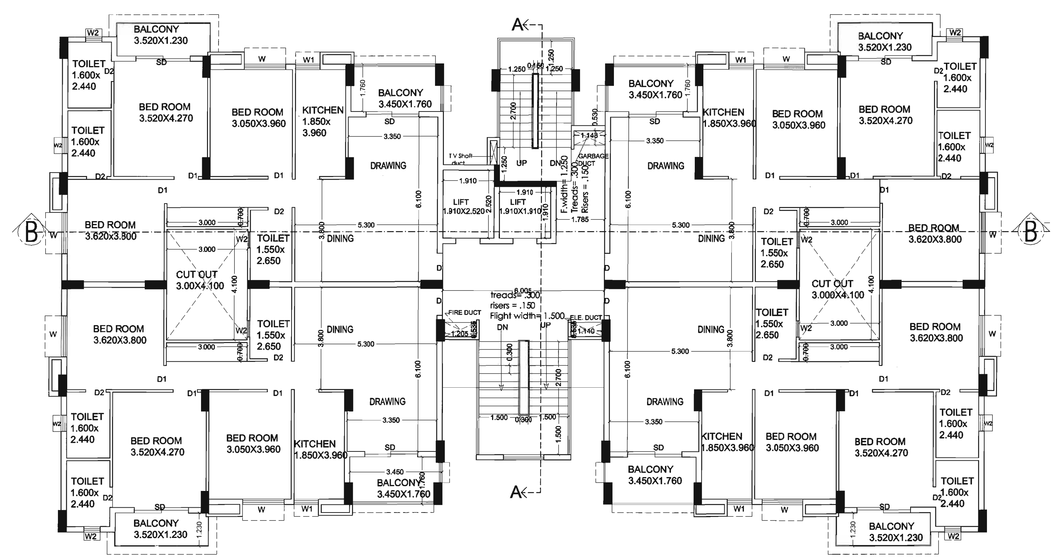

TYPICAL FLOOR PLAN (BLOCK- Q)
1st to 13th Floor

SCHEDULE OF DOORS & WINDOWS

S.NO	TYPE	WIDTH	HEIGHT	CILL. LEV.	LIN. LEV.
1	D	1.05	2.10	0.00	2.10
2	D1	0.90	2.10	0.00	2.10
3	D2	0.75	2.10	0.00	2.10
4	SD	2.00	2.350	0.00	2.350
5	W	1.525	1.60	0.750	2.350
6	W1	1.20	1.300	1.050	2.350
7	W2	0.60	0.90	1.200	2.10

PLOT DETAILS:
KHASRA NO.453,454,454/2,454/1,432,433,478, 479,480,484,485,434,434/735,435,436,437, 437/736,438,439,440,482,500,502,503,504/1 478/716 IN VILLAGE JHAI TEH. SAGANER ON AJMER ROAD ,JAIPUR

Project:-
PROPOSED GROUP HOUSING ASHIANA UMANG

Developer:-
ASHIANA HOUSING LTD.

Sheet title:-
STILT FLOOR PLAN
TYPICAL FLOOR PLAN &
ELEVATIONS

SCALE-1:100 | **BLOCK- Q RESIDENCE** | NORTH variable/site plan

For Ashiana Housing Limited
Authorised Signatory
SIGNATURE OF CLIENT

BISWAJIT SENGUPTA
B.Arch, FIA, AIIID
Regd. Architect : CA/75/886
Regd.Architect : CA/75/886
SIGNATURE OF ARCHITECT

SHEET NO.11/18

SECTION ON B -B

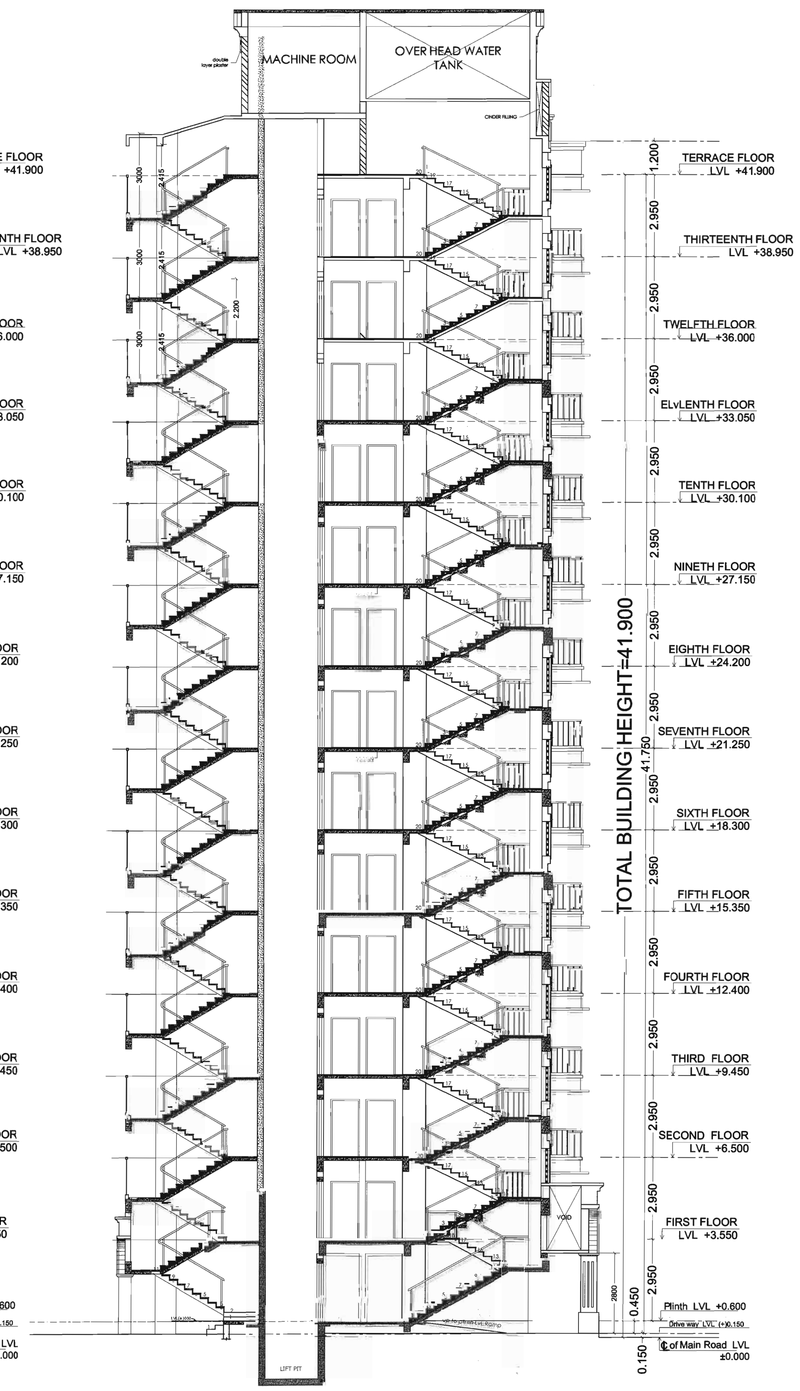

SECTION ON A -A

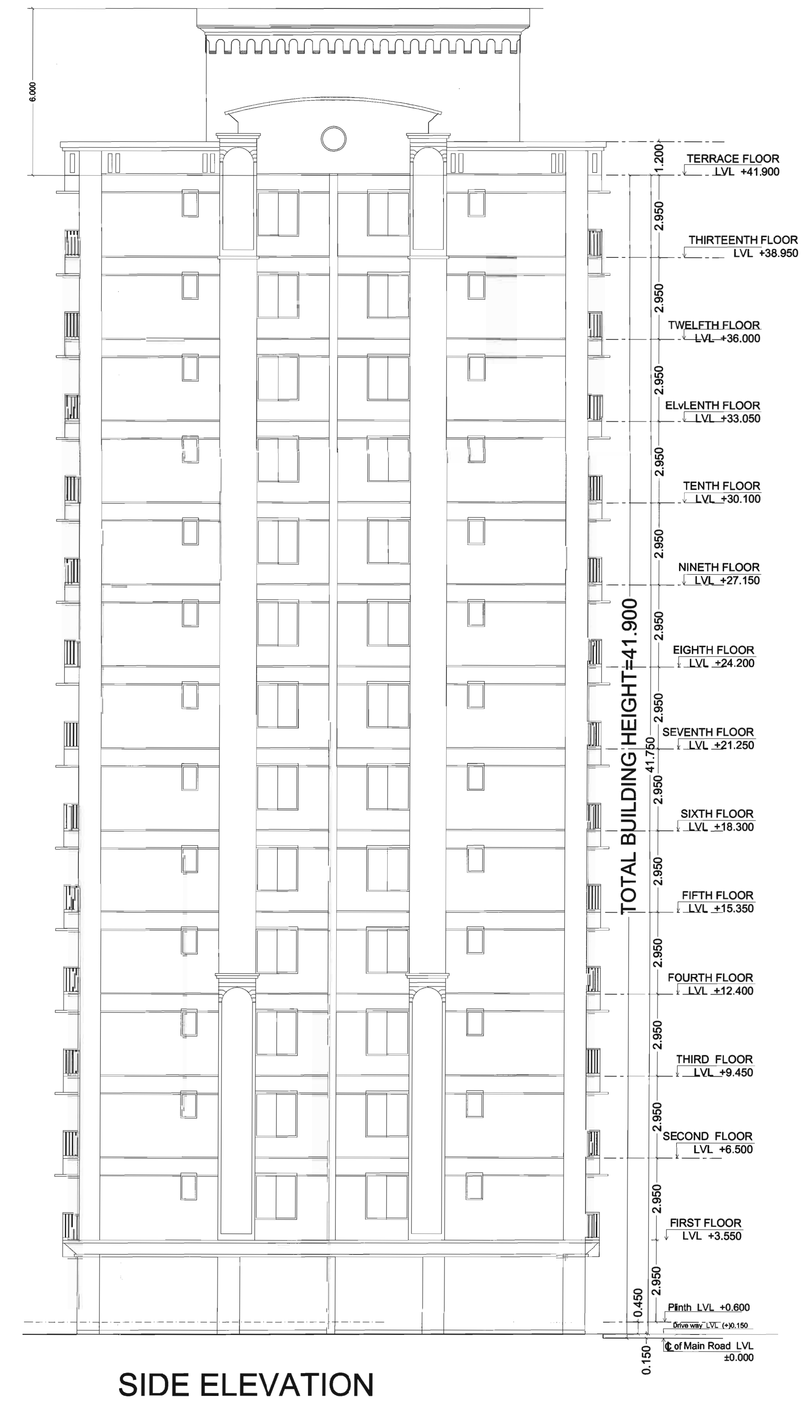

SIDE ELEVATION

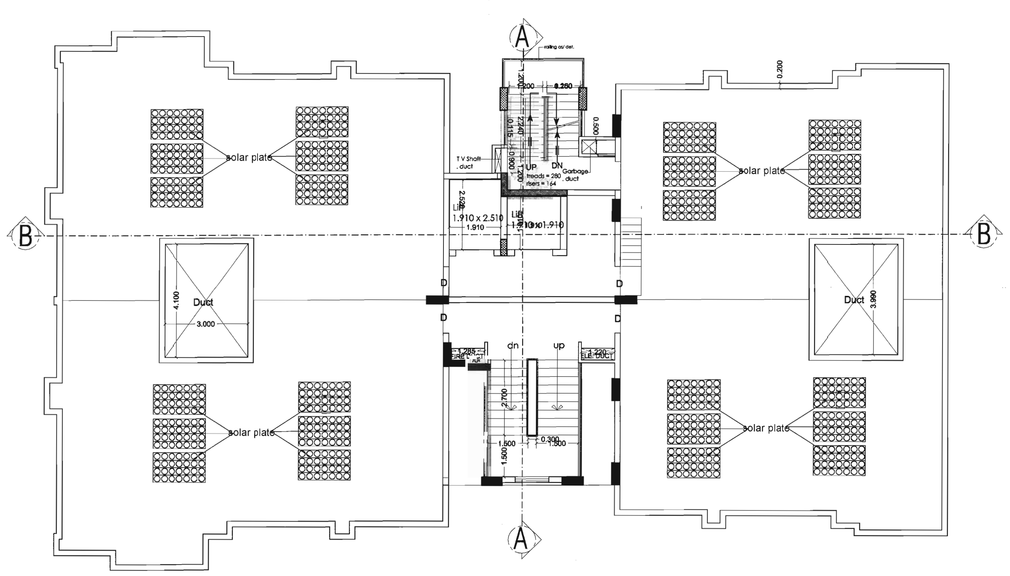

TERRACE FLOOR PLAN

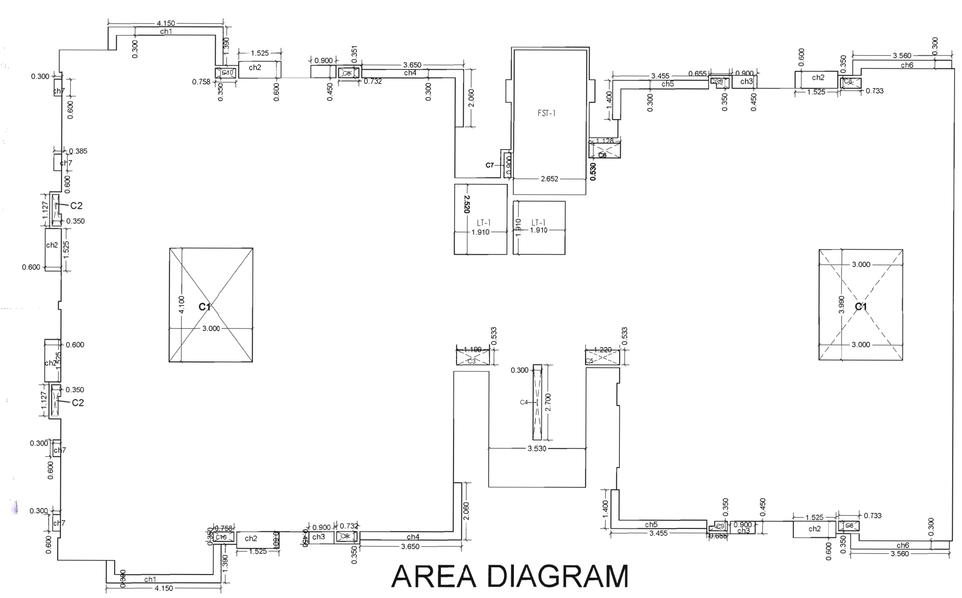

AREA DIAGRAM

BLOCK -R,S

FLOOR NAME	BLOCK AREA	CUT OUT	Gross BUA	CHAJJA	BUILT UP AREA	FIRE STAIR	LIFT	H.A.R.	NO OF UNIT	NO OF BLOCK
BASEMENT										
STILT FLOOR	1,75,19	1.51	84.08	0.00	84.08	0.00	0.00	84.08	0.00	
1st FLOOR	5,36.07	29.78	504.29	19.55	484.74	13.73	8.46	462.50	4.00	
2nd FLOOR	5,36.07	29.78	504.29	19.55	484.74	13.73	8.46	462.50	4.00	
3rd FLOOR	5,36.07	29.78	504.29	19.55	484.74	13.73	8.46	462.50	4.00	
4th FLOOR	5,36.07	29.78	504.29	19.55	484.74	13.73	8.46	462.50	4.00	
5th FLOOR	5,36.07	29.78	504.29	19.55	484.74	13.73	8.46	462.50	4.00	
6th FLOOR	5,36.07	29.78	504.29	19.55	484.74	13.73	8.46	462.50	4.00	
7th FLOOR	5,36.07	29.78	504.29	19.55	484.74	13.73	8.46	462.50	4.00	
8th FLOOR	5,36.07	29.78	504.29	19.55	484.74	13.73	8.46	462.50	4.00	
9th FLOOR	5,36.07	29.78	504.29	19.55	484.74	13.73	8.46	462.50	4.00	
10th FLOOR	5,36.07	29.78	504.29	19.55	484.74	13.73	8.46	462.50	4.00	
11th FLOOR	5,36.07	29.78	504.29	19.55	484.74	13.73	8.46	462.50	4.00	
12th FLOOR	5,36.07	29.78	504.29	19.55	484.74	13.73	8.46	462.50	4.00	
13th FLOOR	5,36.07	29.78	504.29	19.55	484.74	13.73	8.46	462.50	4.00	
TERRACE	86.36		86.36		86.36					
TOTAL	71,14.86	388.05	6726.21	254.15	6472.06	179.14	109.98	6196.50	52.00	2 NOS

PLOT DETAILS:

KHASRA NO.453,454,454/2,454/1,432,433,478, 479,480,484,485,434,434/735,435,436,437, 437/736,438,439,440,482,500,502,503,504/1 478/716 IN VILLAGE JHAI TEH. SAGANER ON AJMER ROAD ,JAIPUR

Project:-

PROPOSED GROUP HOUSING ASHIANA UMANG

Developer:-

ASHIANA HOUSING LTD.

Sheet title:-

TERRACE FLOOR PLAN
AREA DIAGRAM
ELEVATIONS & SECTION

SCALE-1:100 | **BLOCK-R&S RESIDENCE** | NORTH variable/site plan

For Ashiana Housing Limited
Authorised Signatory

BISWAJIT SENGUPTA
B.Arch, FIIA, AIID
Regd. Architect : CA/75/886

SIGNATURE OF CLIENT | SIGNATURE OF ARCHITECT

SHEET NO.12/18

FRONT ELEVATION

REAR SIDE ELEVATION

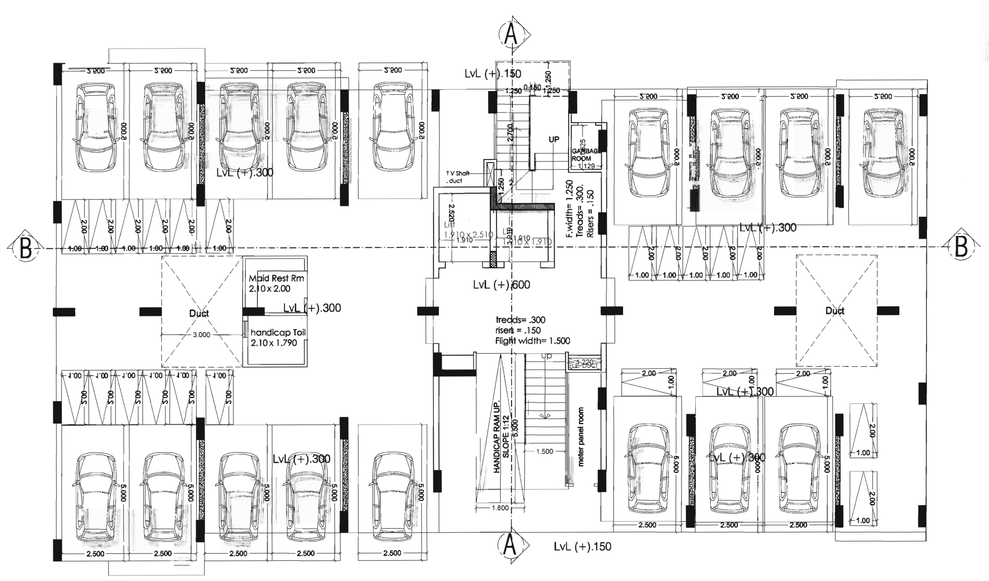

GROUND FLOOR PLAN

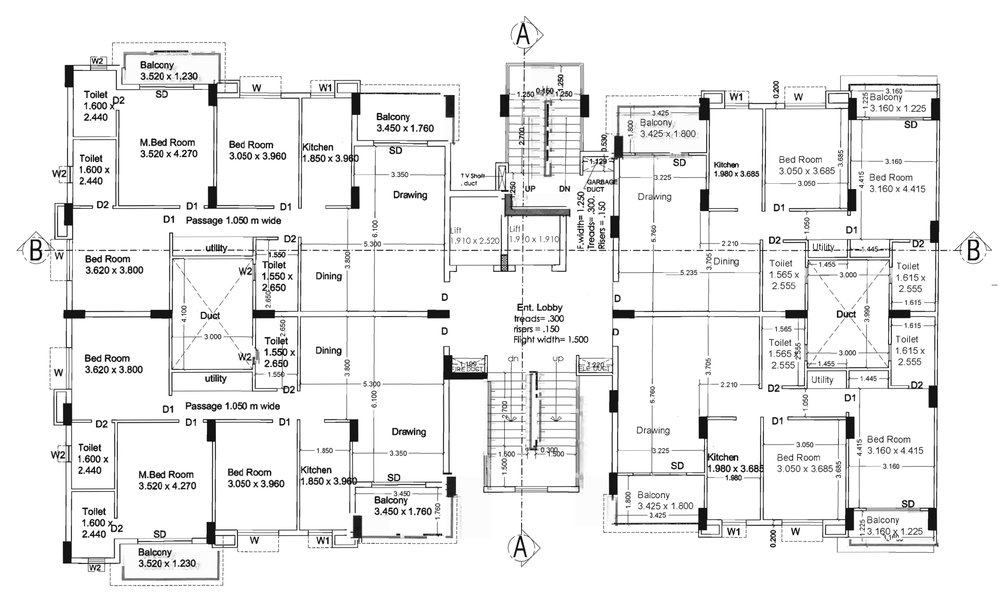

TYPICAL FLOOR PLAN
1st to 13th FLOOR

SCHEDULE OF DOORS & WINDOWS

S.NO	TYPE	WIDTH	HEIGHT	CILL. LEV.	LIN. LEV.
1	D	1.05	2.10	0.00	2.10
2	D1	0.90	2.10	0.00	2.10
3	D2	0.75	2.10	0.00	2.10
4	SD	2.00	2.350	0.00	2.350
5	W	1.525	1.60	0.750	2.350
6	W1	0.90	1.300	1.050	2.350
7	W2	0.60	0.90	1.200	2.10

PLOT DETAILS:
KHASRA NO.453,454,454/2,454/1,432,433,478, 479,480,484,485,434,434/735,435,436,437, 437/736,438,439,440,482,500,502,503,504/1 478/716 IN VILLAGE JHAI TEH. SAGANER ON AJMER ROAD ,JAIPUR

Project:-
PROPOSED GROUP HOUSING ASHIANA UMANG

Developer:-
ASHIANA HOUSING LTD.

Sheet title:-
STILT FLOOR PLAN
TYPICAL FLOOR PLAN
& ELEVATIONS

SCALE-1:100 | BLOCK-R&S RESIDENCE | NORTH variable/site plan

For Ashiana Housing Limited
Authorised Signatory
SIGNATURE OF CLIENT

BISWAJIT SENGUPTA
B.Arch, FIIA, AIIID
Regd. Architect : CA/75/886
Regd.Architect : CA/75/886
SIGNATURE OF ARCHITECT



SECTION ON B -B

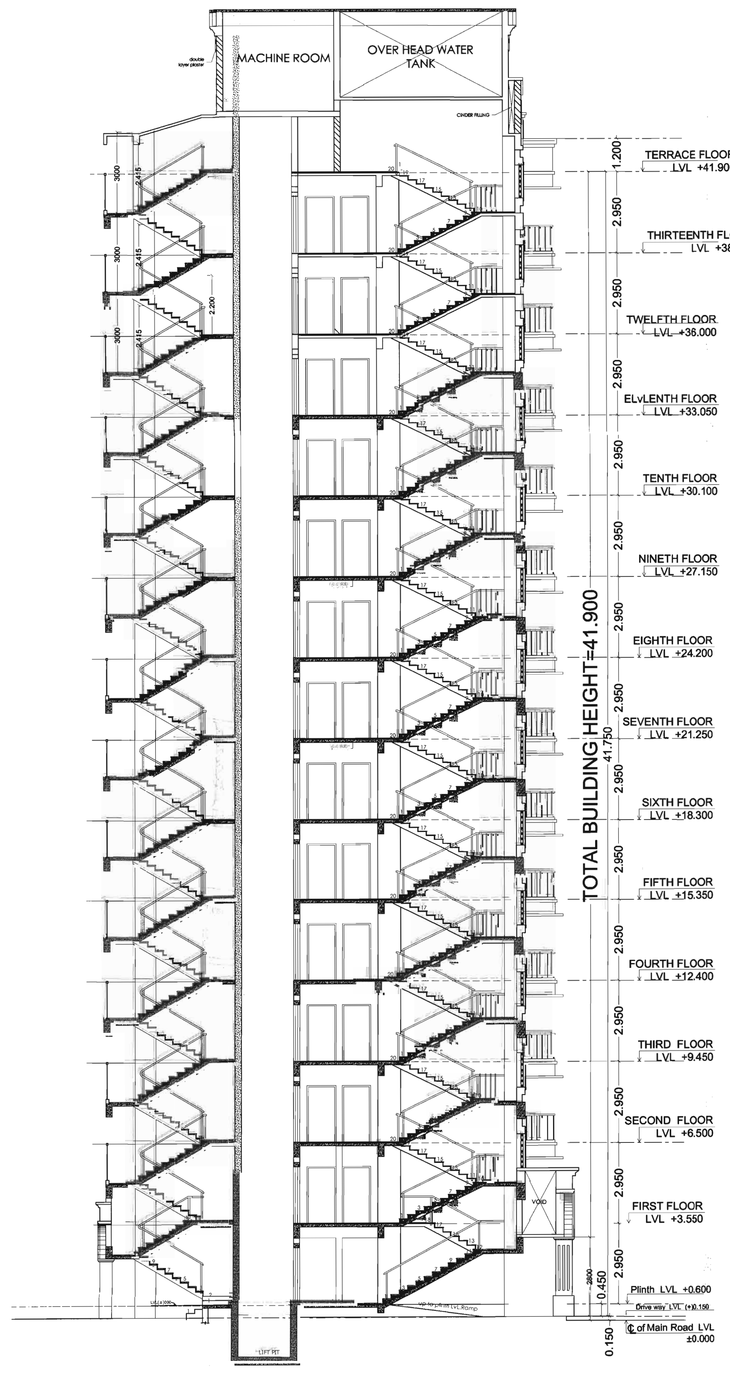

SECTION ON A -A



SIDE ELEVATION

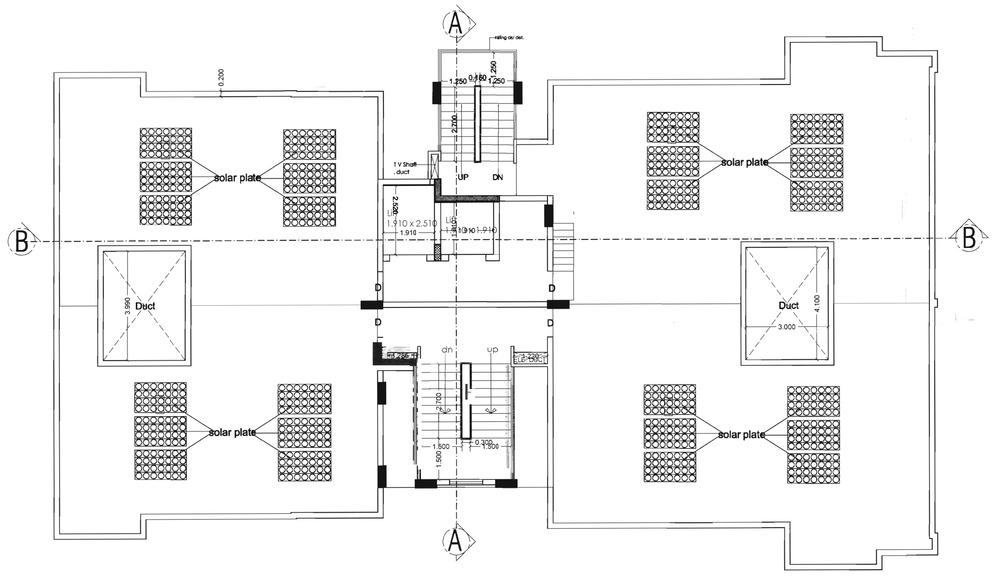

TERRACE FLOOR PLAN

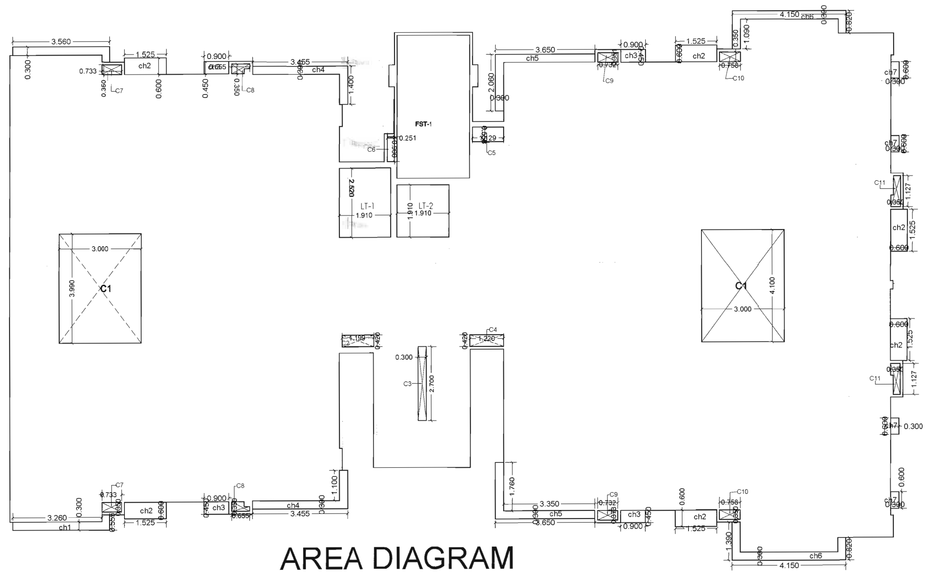

AREA DIAGRAM

BLOCK -R1,S3											
FLOOR NAME	BLOCK AREA	CUTOUT	Gross B.U.A	CHAJJA	BUILT UP AREA	FIRE STAIR	LIFT	F.A.R	NO OF UNIT	NO OF BLOCK	
BASEMENT											
STILT FLOOR	91.62	1.24	90.38	0.00	90.38	0.00	0.00	90.38			
1st FLOOR	534.82	29.53	504.53	19.50	484.96	13.78	8.46	462.72	4.00		
2nd FLOOR	534.82	29.53	504.53	19.50	484.96	13.78	8.46	462.72	4.00		
3rd FLOOR	534.82	29.53	504.53	19.50	484.96	13.78	8.46	462.72	4.00		
4th FLOOR	534.82	29.53	504.53	19.50	484.96	13.78	8.46	462.72	4.00		
5th FLOOR	534.82	29.53	504.53	19.50	484.96	13.78	8.46	462.72	4.00		
6th FLOOR	534.82	29.53	504.53	19.50	484.96	13.78	8.46	462.72	4.00		
7th FLOOR	534.82	29.53	504.53	19.50	484.96	13.78	8.46	462.72	4.00		
8th FLOOR	534.82	29.53	504.53	19.50	484.96	13.78	8.46	462.72	4.00		
9th FLOOR	534.82	29.53	504.53	19.50	484.96	13.78	8.46	462.72	4.00		
10th FLOOR	534.82	29.53	504.53	19.50	484.96	13.78	8.46	462.72	4.00		
11th FLOOR	534.82	29.53	504.53	19.50	484.96	13.78	8.46	462.72	4.00		
12th FLOOR	534.82	29.53	504.53	19.50	484.96	13.78	8.46	462.72	4.00		
13th FLOOR	534.82	29.53	504.53	19.50	484.96	13.78	8.46	462.72	4.00		
TERRACE	85.27		85.27		85.27						
TOTAL	7139.35	384.87	6754.28	254.15	6500.13	179.14	109.98	6205.74	52.00	2 NOS	

SHEET NO.15/18

PLOT DETAILS:

KHASRA NO.453,454,454/2,454/1,432,433,478, 479,480,484,485,434,434/735,435,436,437, 437/736,438,439,440,482,500,502,503,504/1 478/716 IN VILLAGE JHAI TEH. SAGANER ON AJMER ROAD ,JAIPUR

Project:-

PROPOSED GROUP HOUSING ASHIANA UMANG

Developer:-

ASHIANA HOUSING LTD.

Sheet title:-

TERRACE FLOOR PLAN
AREA DIAGRAM
ELEVATIONS & SECTION

SCALE-1:100

BLOCK-R1&S3
RESIDENCE

NORTH
variable/site plan

Per Ashiana Housing Limited
Authorised Signatory

SIGNATURE OF CLIENT

BISWAJIT SENGUPTA
B.Arch, FIIA, AIID
Regd. Architect : CA/75/886

Regd.Architect : CA/75/886

SIGNATURE OF ARCHITECT

SHEET NO.16/18

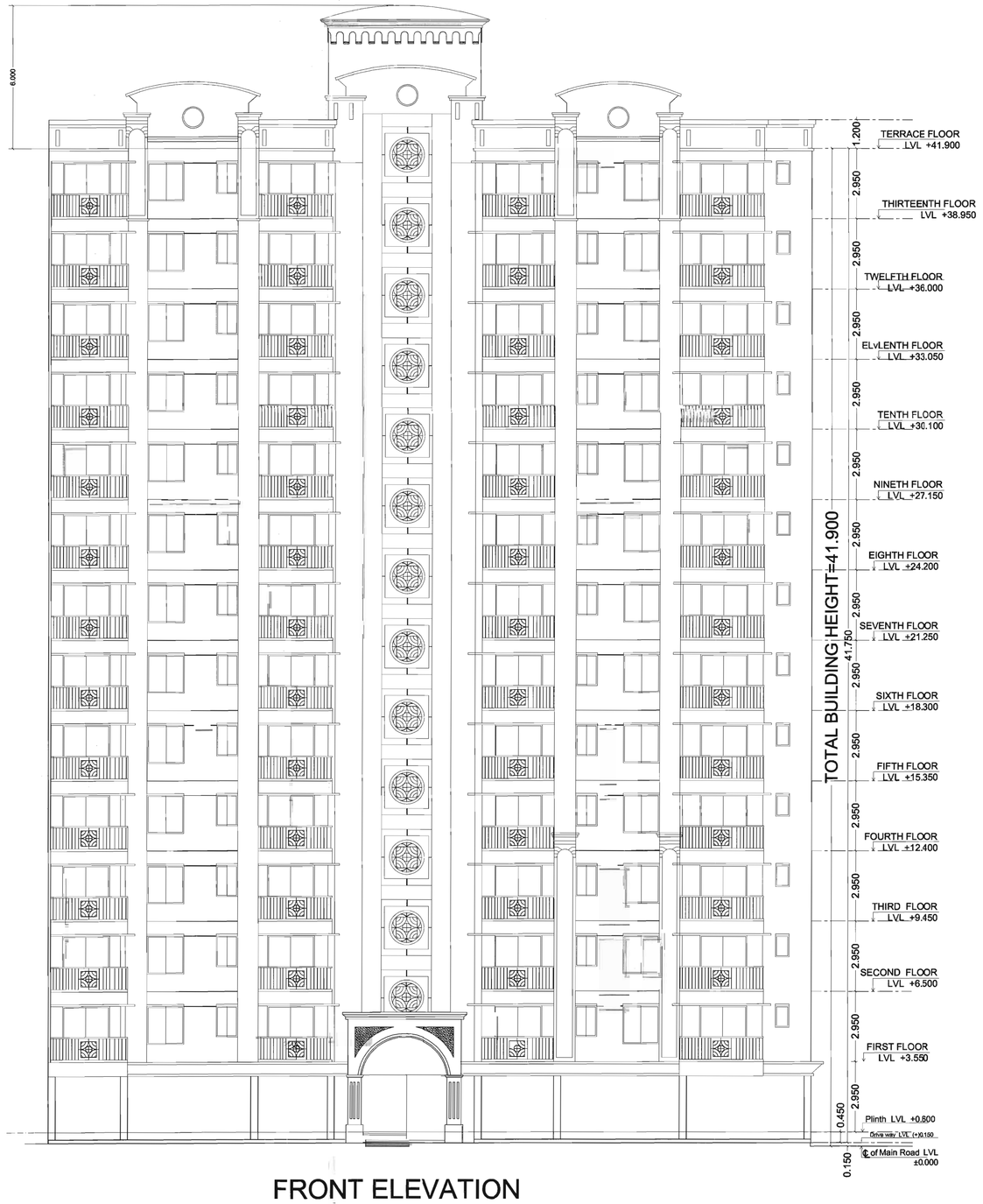

FRONT ELEVATION

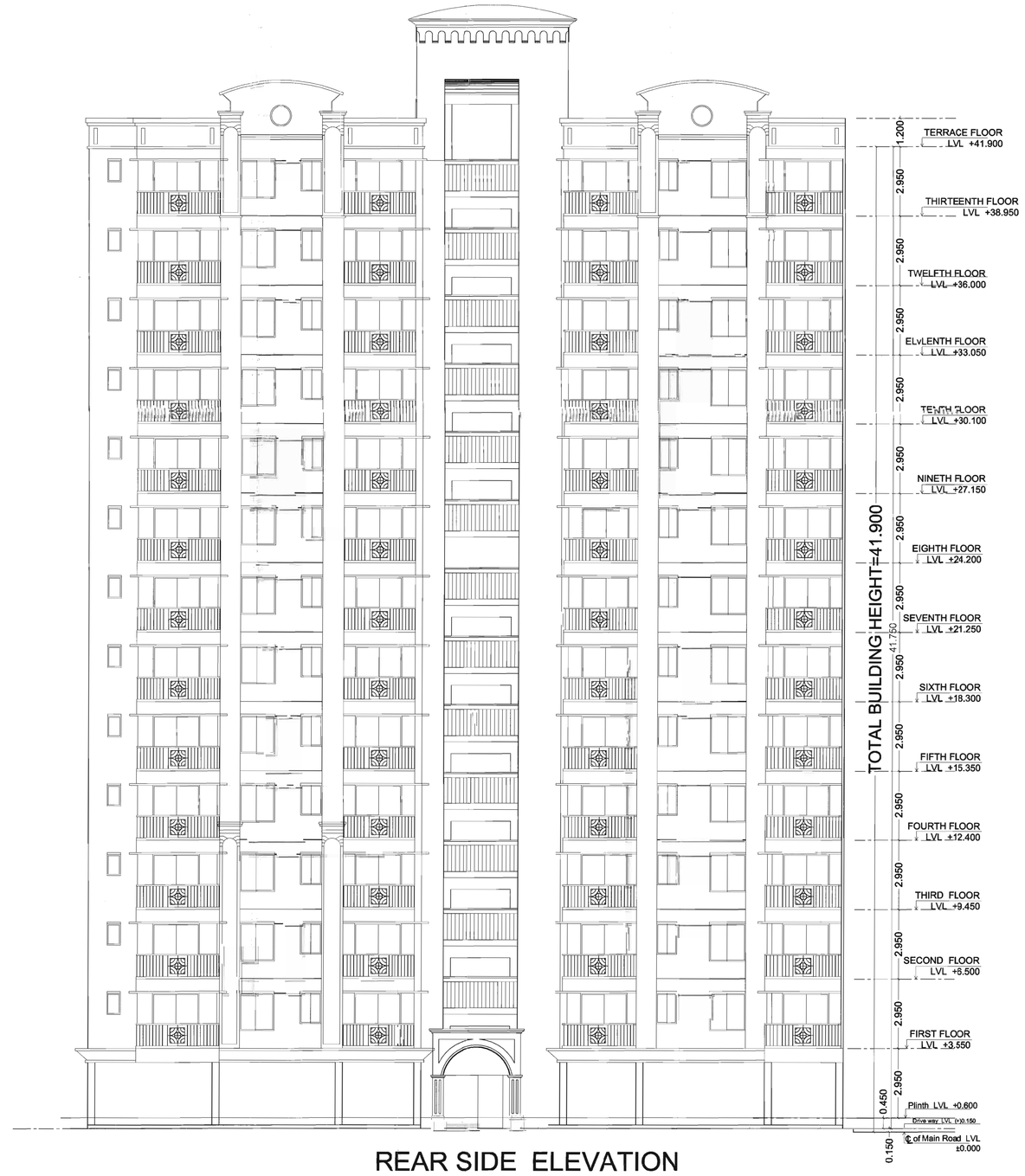

REAR SIDE ELEVATION

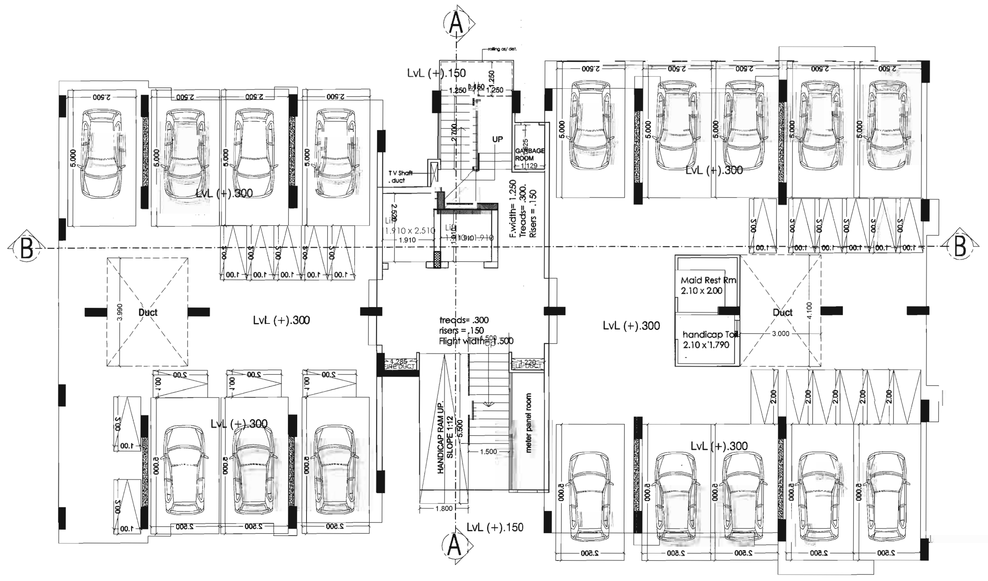

GROUND FLOOR PLAN

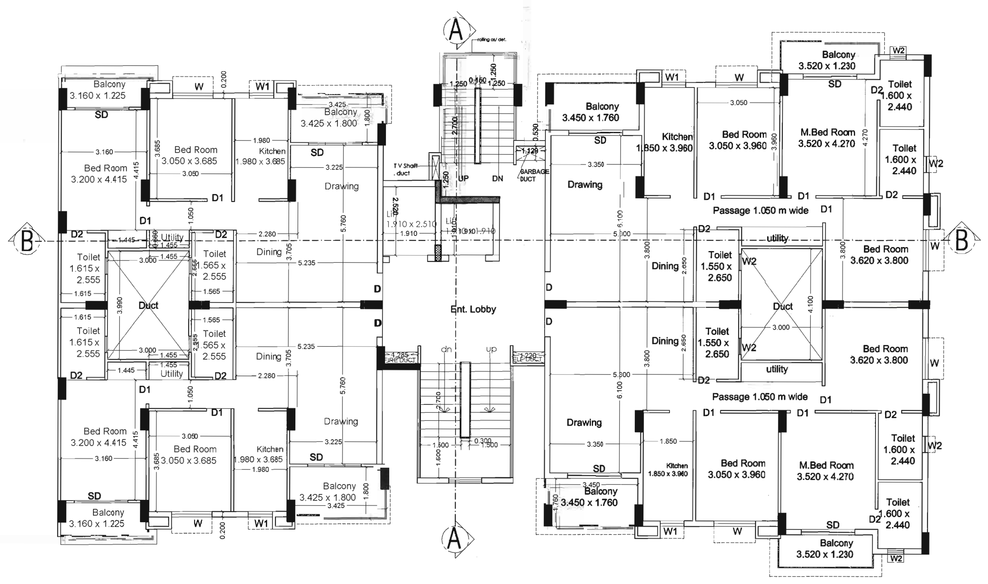

TYPICAL FLOOR PLAN
1st to 13th FLOOR

SCHEDULE OF DOORS & WINDOWS

S.NO	TYPE	WIDTH	HEIGHT	CILL. LEV.	LIN. LEV.
1	D	1.05	2.10	0.00	2.10
2	D1	0.90	2.10	0.00	2.10
3	D2	0.75	2.10	0.00	2.10
4	SD	2.00	2.350	0.00	2.350
5	W	1.525	1.60	0.750	2.350
6	W1	0.90	1.300	1.050	2.350
7	W2	0.60	0.90	1.200	2.10

PLOT DETAILS:
KHASRA NO.453,454,454/2,454/1,432,433,478, 479,480,484,485,434,434/735,435,436,437, 437/736,438,439,440,482,500,502,503,504/1 478/716 IN VILLAGE JHAI TEH. SAGANER ON AJMER ROAD ,JAIPUR

Project:-
PROPOSED GROUP HOUSING ASHIANA UMANG

Developer:-
ASHIANA HOUSING LTD.

Sheet title:-
STILT FLOOR PLAN
TYPICAL FLOOR PLAN
& ELEVATIONS

SCALE-1:100

BLOCK-R1&S3 RESIDENCE

NORTH
variable/site plan

For Ashiana Housing Limited
Authorised Signatory
SIGNATURE OF CLIENT

BISWAJIT SENGUPTA
B.Arch, FIA, AIIID
Regd. Architect : CA/75/886
Regd.Architect : CA/75/886
SIGNATURE OF ARCHITECT